


简明 世界史地图

北京大学历史系
简明世界史编写组



简明世界史地图

(征求意见稿)

北京大学历史系简明世界史编写组

人 民 出 版 社

简明世界史地图

(征求意见稿)

北京大学历史系简明世界史编写组

*

人民出版社出版 新华书店发行

中国人民解放军一二〇五厂印刷

850×1168 毫米 32 开本 2 印张

1975 年 12 月第 1 版 1975 年 12 月北京第 1 次印刷

书号 11001·300 定价 0.40 元

(内部发行)

编者说明

我们在编写《简明世界史》的过程中，同时编辑了这册示意图，作为该书的附录，供教学参考用。

由于我们水平不高，时间仓促，图中难免有不当之处，诚恳地希望读者提出宝贵意见，以便今后改正。

本图册中国国界线系根据地图出版社出版的《中华人民共和国地图》绘制。

北京大学历史系简明世界史编写组

一九七五年九月

目 录

古 代 部 分

亚、非、欧古代各大文明发源地(约公元前 1600 年)	2
爱琴海古代文明和西亚、北非的关系	3
马其顿东侵及其后的西亚和北非(迄公元前三世纪中叶)	4
斯巴达克起义	5
二世纪的亚、非、欧古代文明世界	6
亚欧大陆民族大迁徙(迄公元五世纪)	7
张骞西行路线	8
玄奘西行路线(627—645 年)	9
九世纪的伊斯兰教国家	10
十三世纪末的亚洲	11
西班牙入侵前美洲印第安人三大文明区	12
外族入侵下的罗马帝国(350—450 年)	13
十五世纪末的欧洲经济	14
郑和西航线(1405—1433 年)	15
新航路的探索	16
德国农民战争	17
朝中两国反对日本侵略的战争(1592—1598 年)	18

近 代 部 分

十七世纪英国资产阶级革命	20
--------------------	----

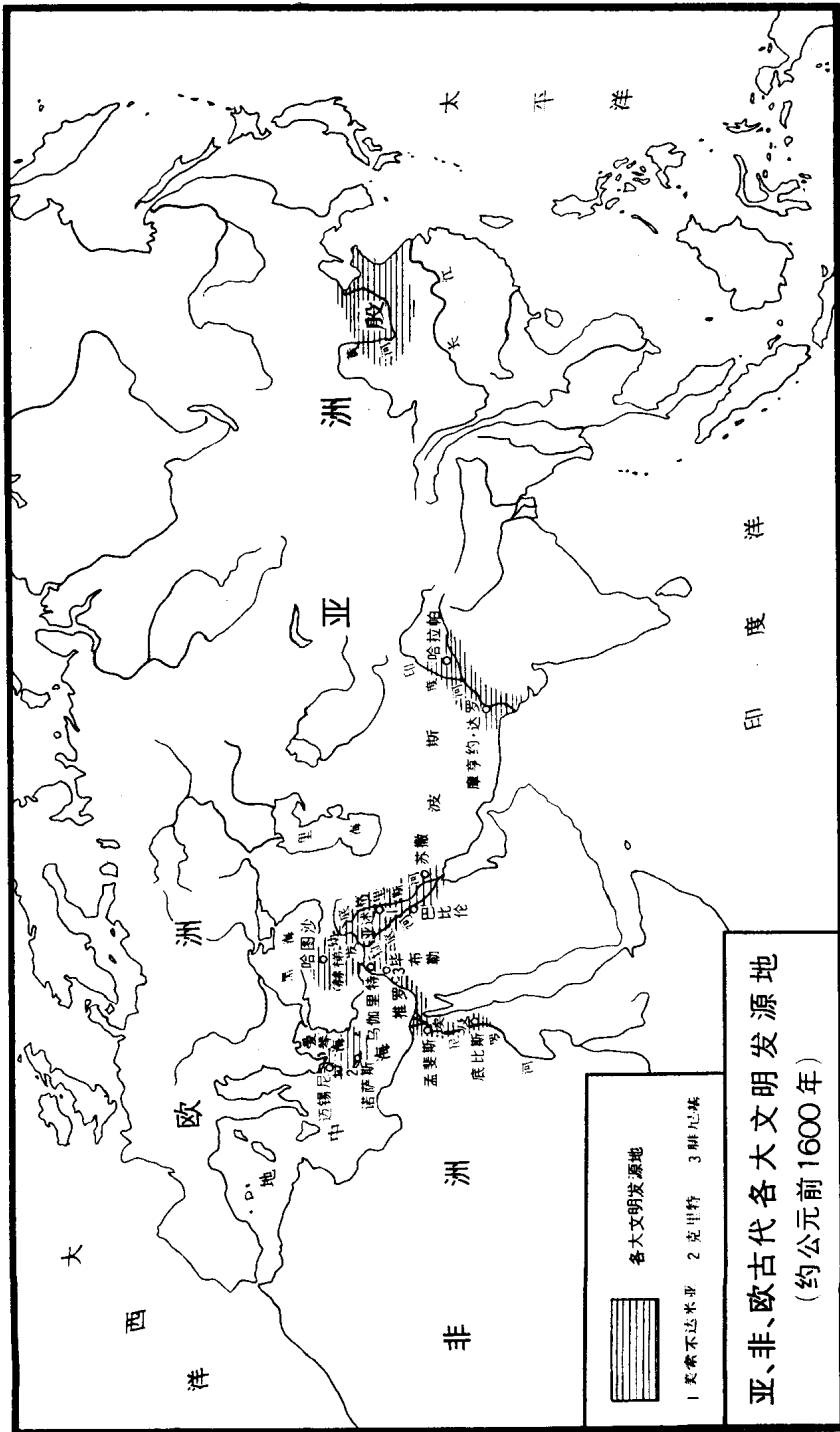
1792—1794 年的法国	21
拿破仑帝国疆界(1812 年)	22
维也纳会议后的欧洲各国(1815 年)	23
十九世纪初的拉丁美洲	24
西山起义(1771—1802 年)	25
1848—1849 年欧洲革命	26
印度民族大起义(1857—1859 年)	27
十八世纪末到十九世纪六十年代的美国领土扩张	28
十九世纪中叶日本的反幕府斗争	29
意大利的统一	30
德意志的统一	31
巴黎公社(1871 年 3 月 18 日—5 月 28 日)	32
1882 年英国武装进攻埃及和埃及军民抗战	33
1885 年帝国主义对非洲的占领	34
朝鲜农民战争(1894—1895 年)	35
印度支那人民抗法斗争(十九世纪末到二十世纪初)	36
1898—1906 年的菲律宾(1898 年前由西班牙占领, 1898 年后由美国占领)	37
1905—1911 年伊朗革命	38
帝国主义瓜分下的非洲(迄 1914 年)	39
1910—1917 年墨西哥革命	40
第一次世界大战前夕的巴尔干半岛	41
第一次世界大战	42

现代部分

彼得格勒十月武装起义(1917 年 11 月)	44
-------------------------------	----

布列斯特和约(1918年3月3日)	45
协约国第一、二次武装干涉的失败	46
协约国第三次武装干涉的失败	47
凡尔赛和约后欧洲疆界的变化	48
朝鲜三一人民起义形势图	49
印度的民族解放运动(1919—1929年)	50
1930—1931年越南革命高潮形势图	51
德国法西斯的扩张	52
1939年9月至1941年6月欧洲形势	53
第二次世界大战的欧洲和北非战场	54
第二次世界大战的太平洋战场	55

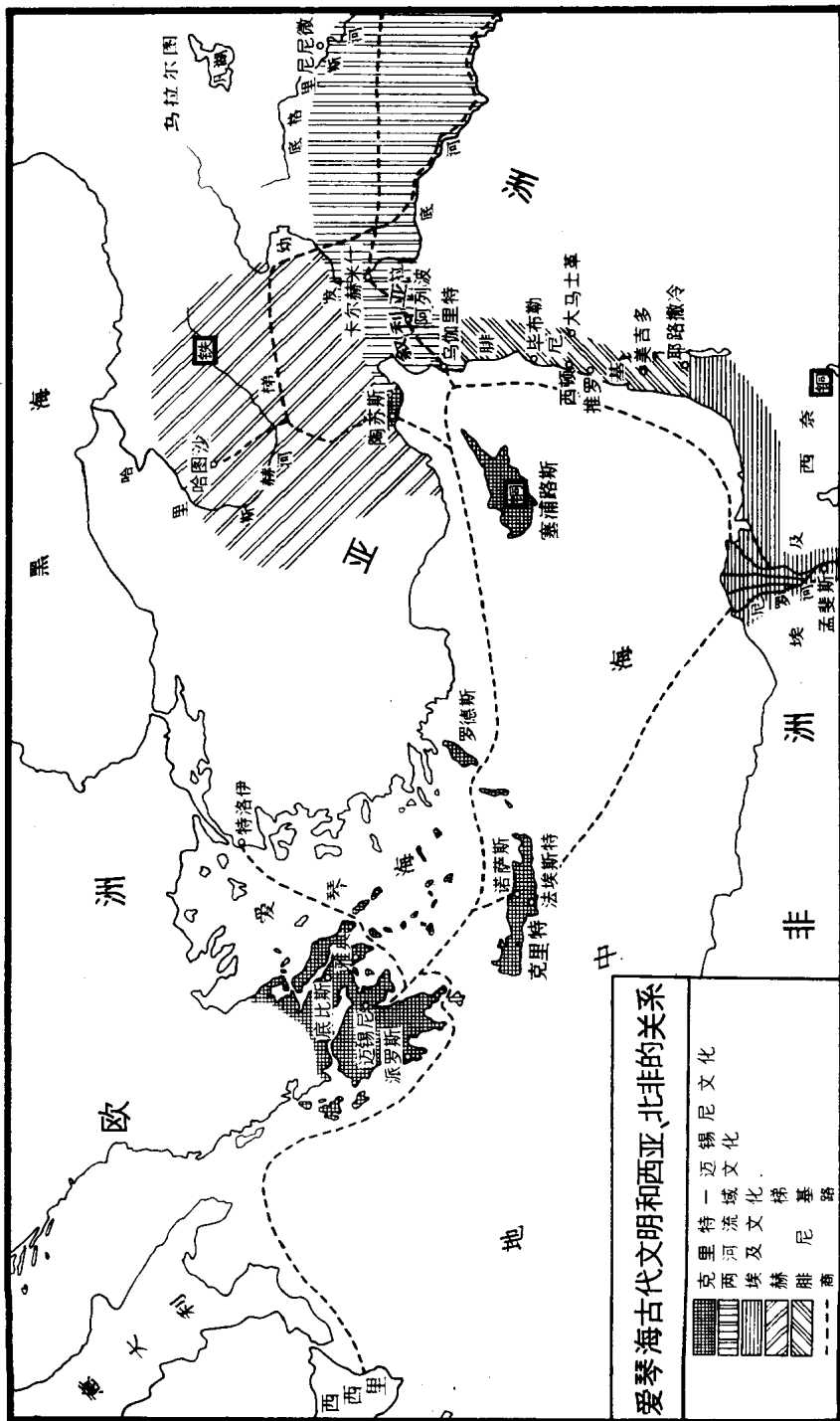
古代部分



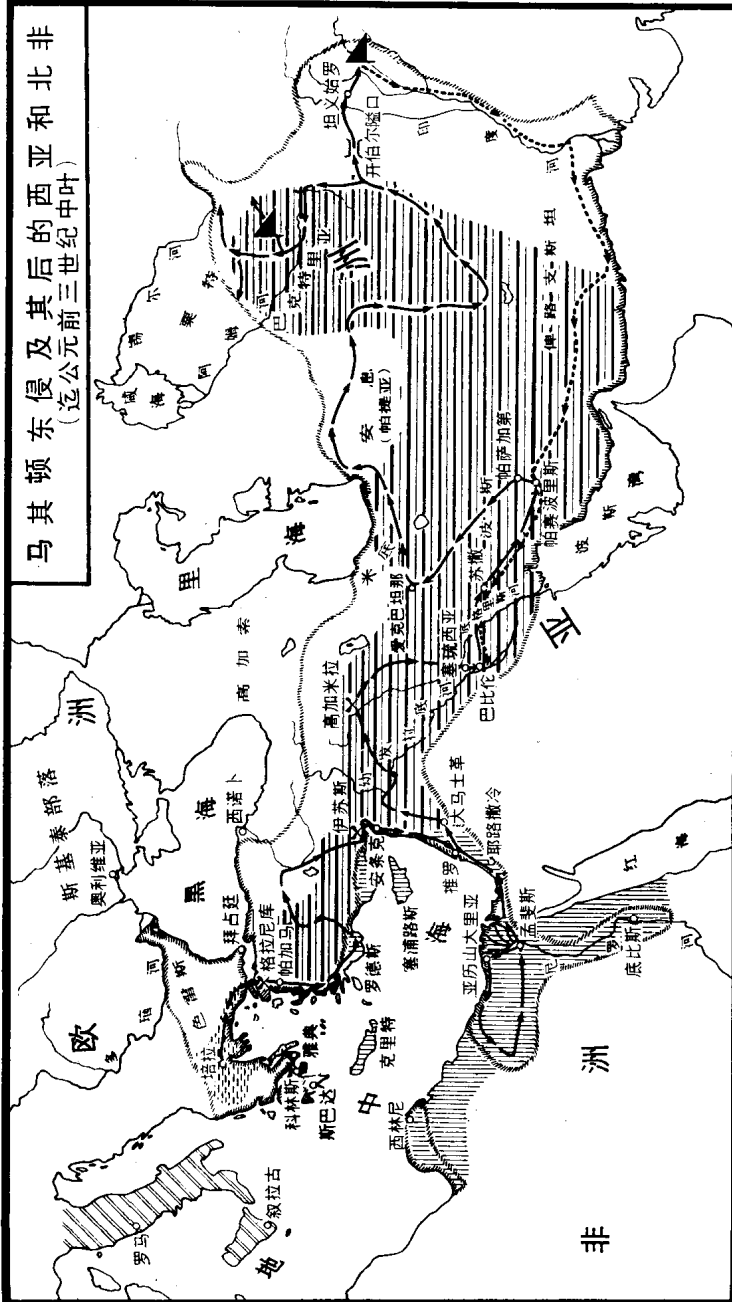
各大文明发源地










- 1 美索不达米亚
- 2 克里特
- 3 哈拉帕

亚、非、欧古代各大文明发源地
(约公元前1600年)



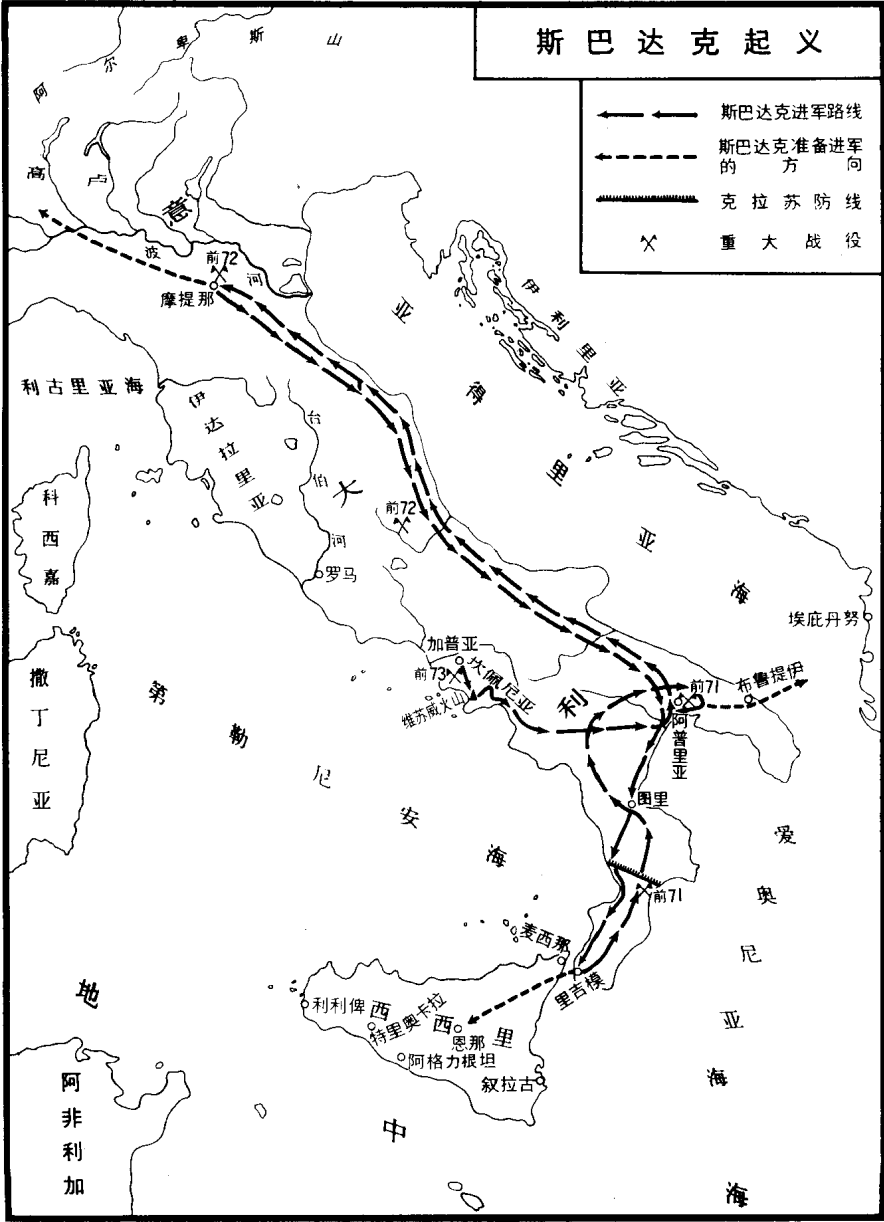
马其顿东侵及其后的西亚和北非 (迄公元前三世中叶)

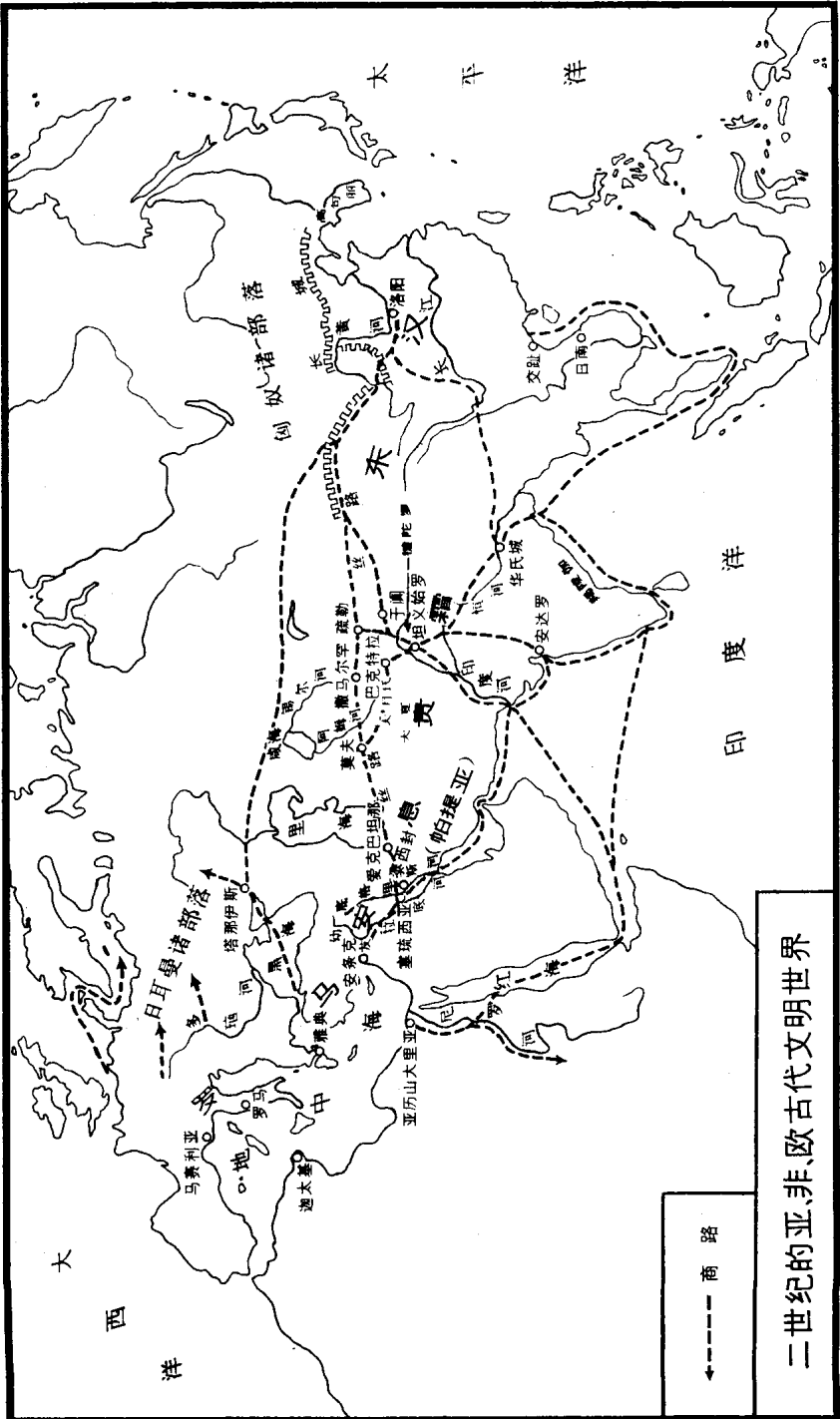


-  马其顿帝国控制线
-  马其顿安提柯王朝辖境
-  埃及托勒密王朝辖境
-  西亚塞琉古王朝辖境
-  罗马辖境
-  马其顿军东侵路线
-  马其顿军与波斯军的重大战役
-  马其顿军遭受被侵略民族激烈抵抗的地区
-  马其顿侵略军被迫退兵路线

斯巴达克起义

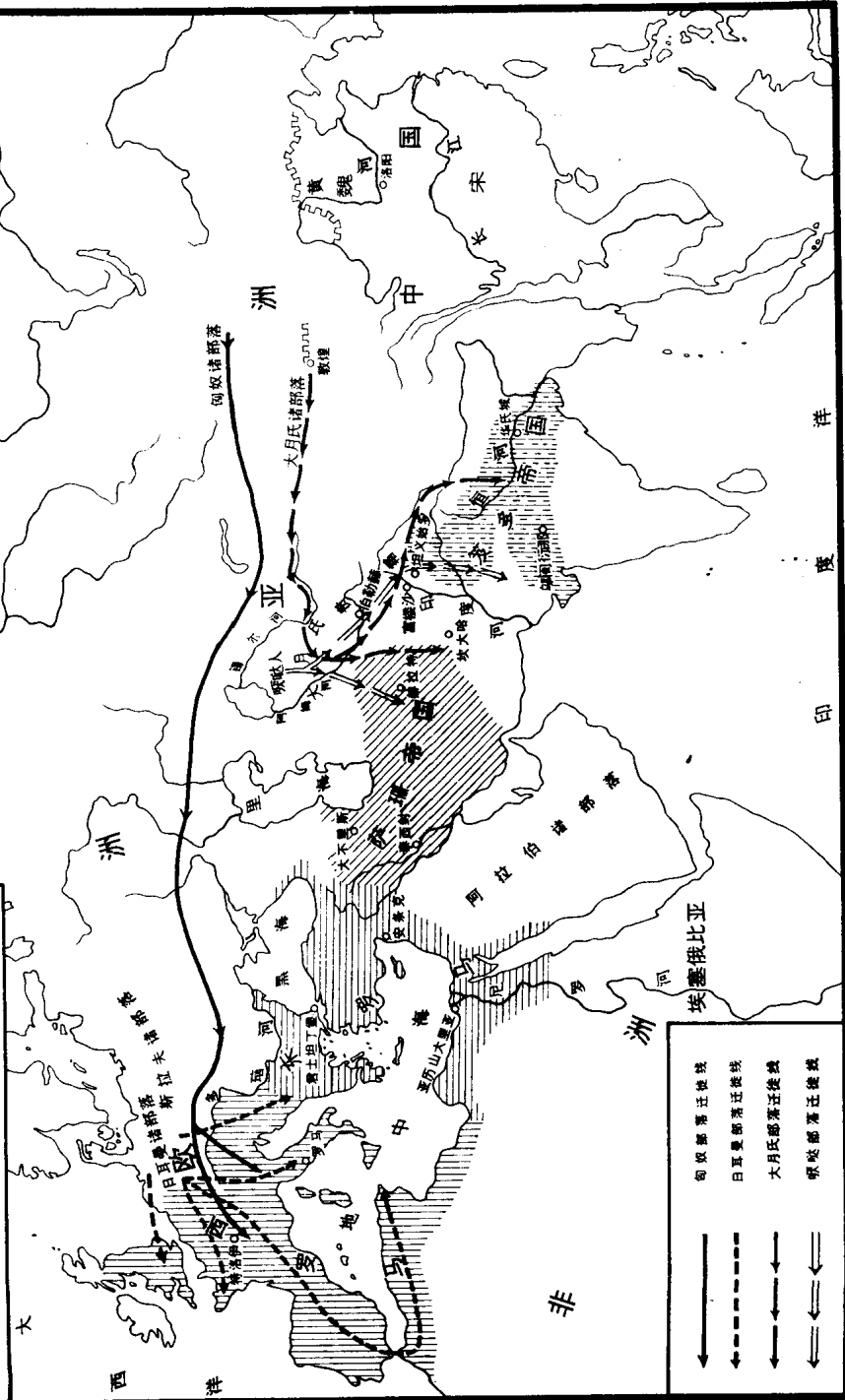
- ← ← 斯巴达克进军路线
- 斯巴达克准备进军的方向
- 克拉苏防线
- × 重大战役



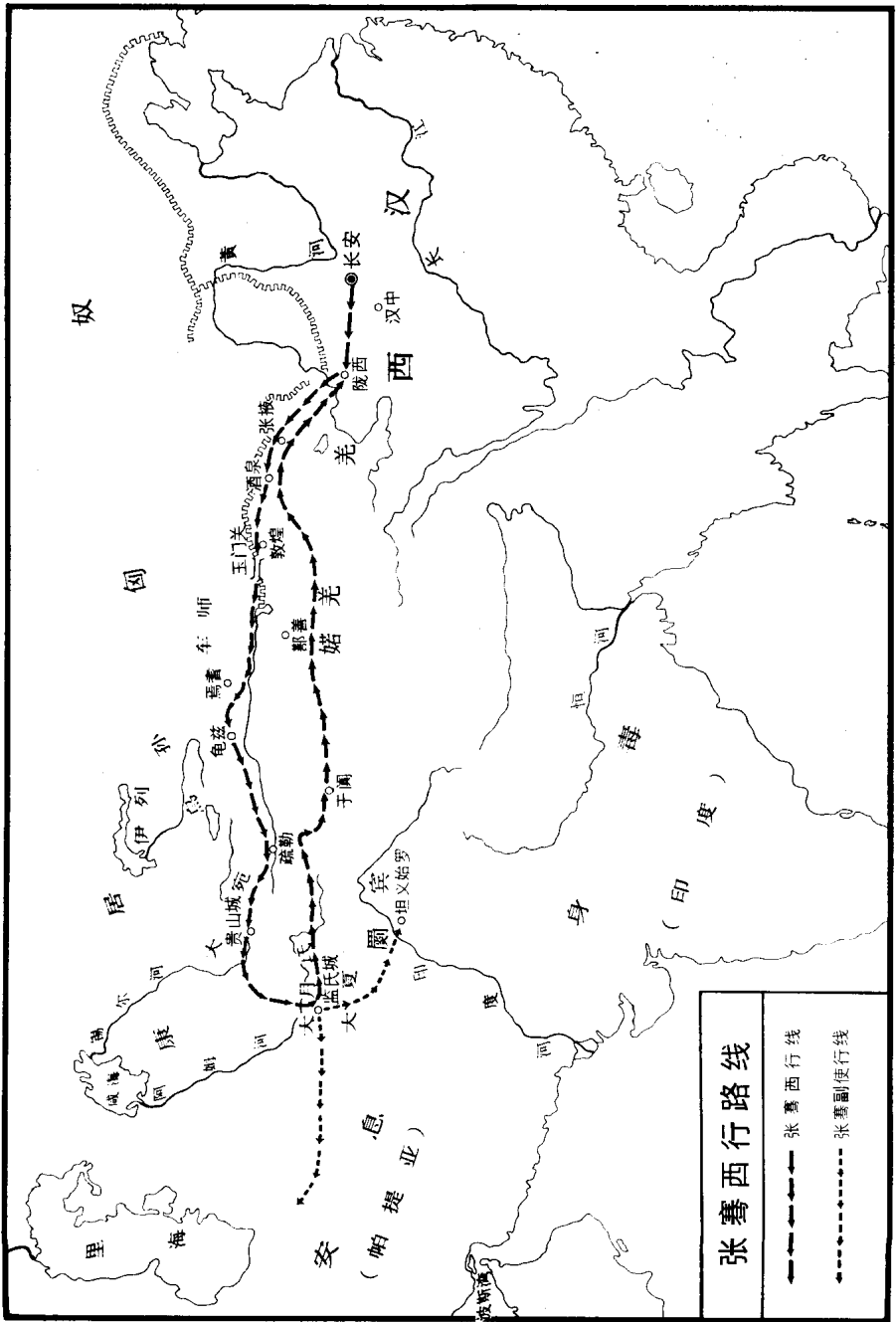


二世纪的亚、非、欧古代文明世界

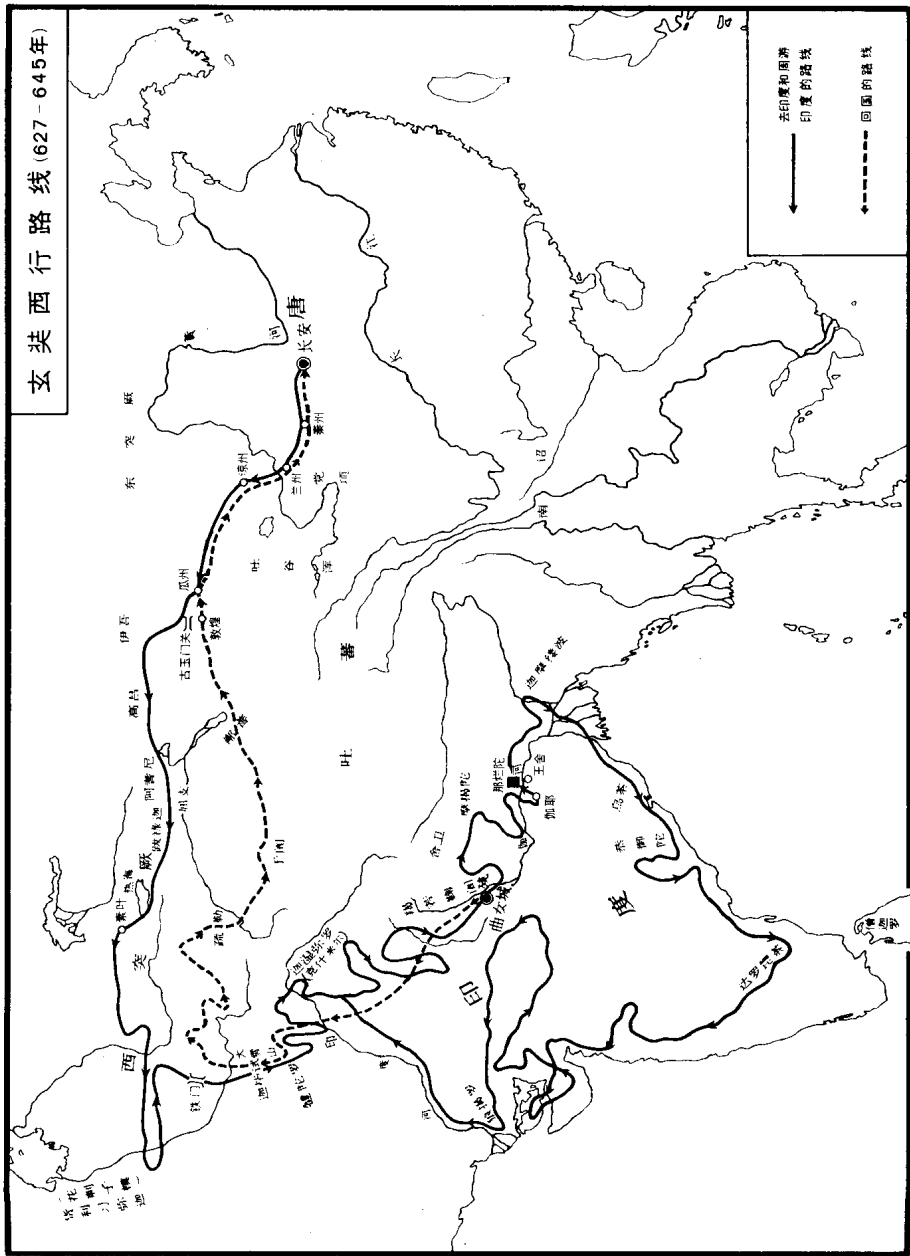
亚欧大陆民族大迁徙(迄公元五世纪)

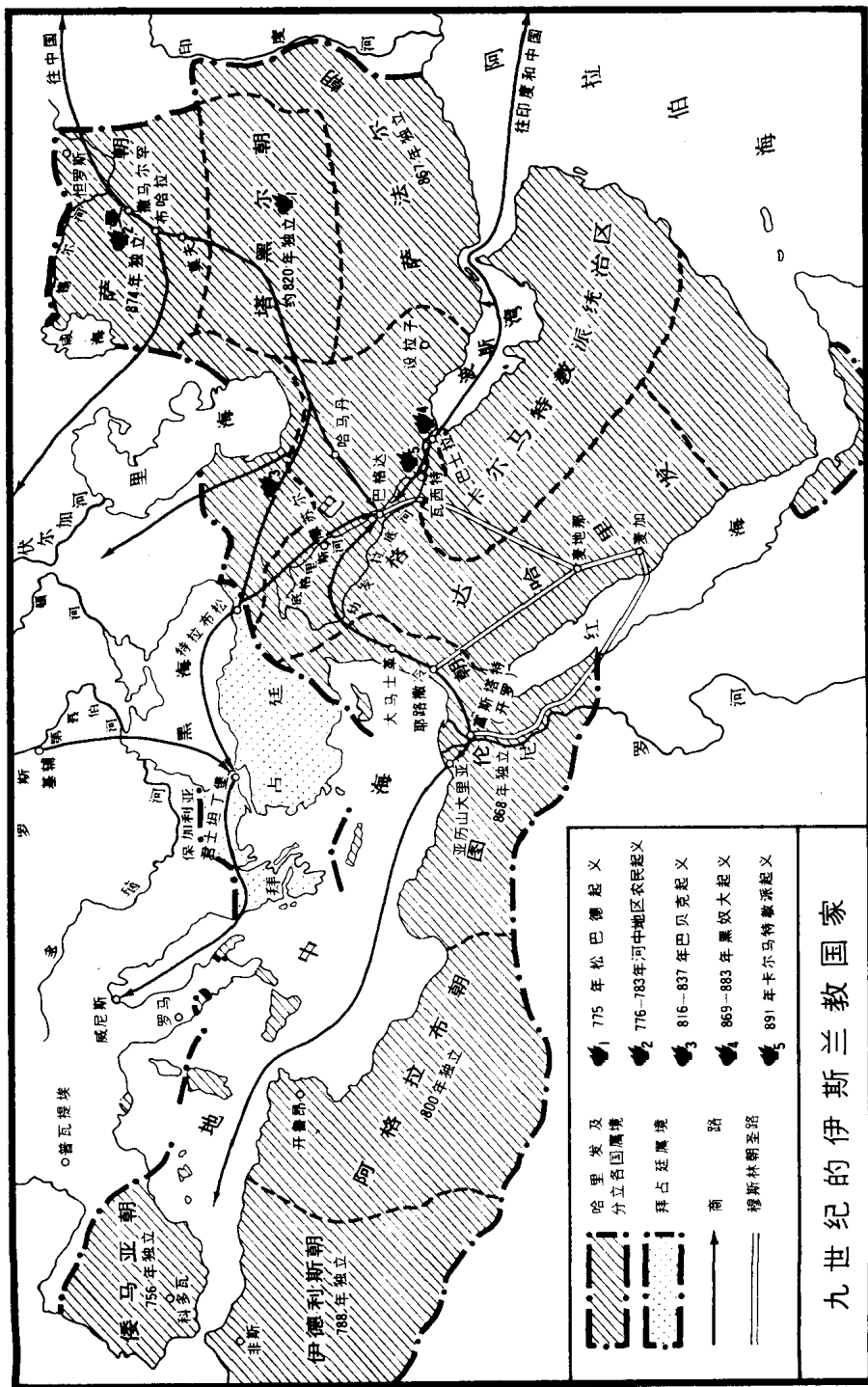


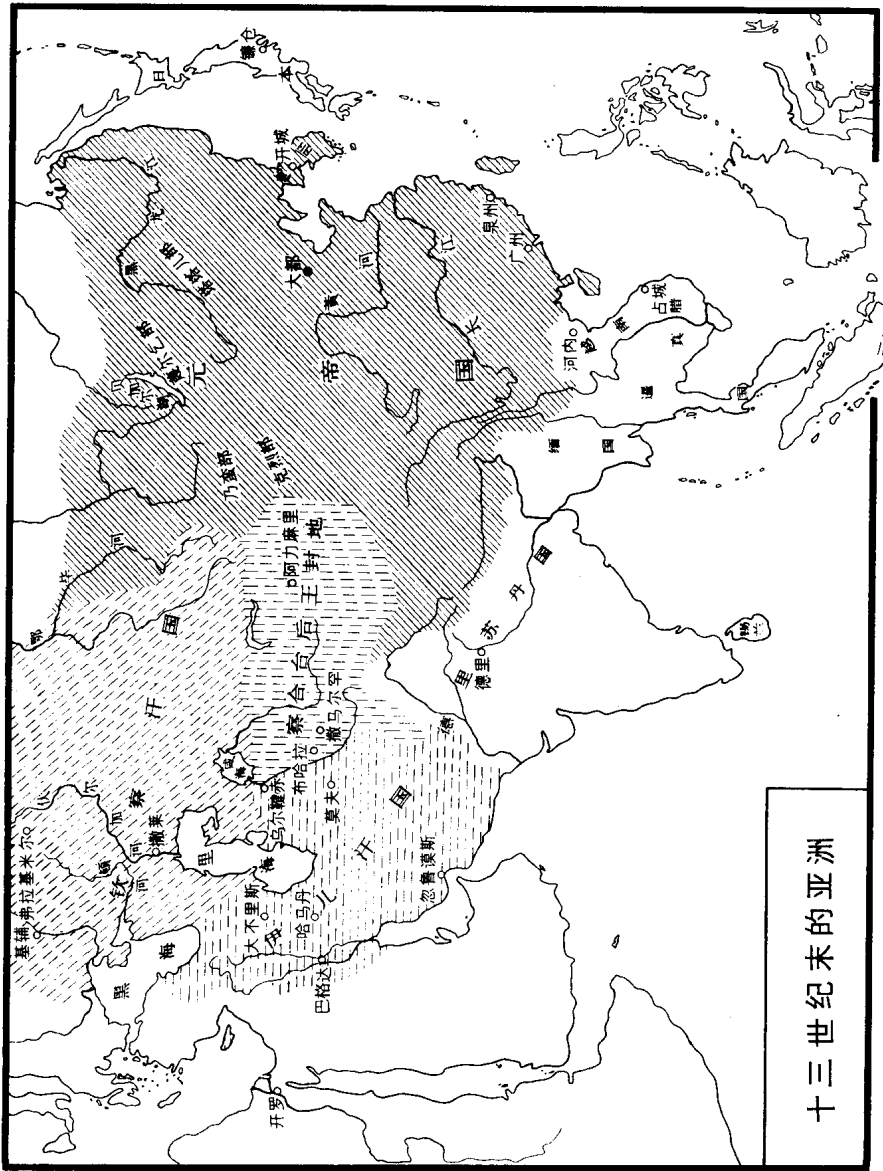
	匈奴部落迁徙线
	鲜卑部落迁徙线
	大月氏部落迁徙线
	匈部落迁徙线



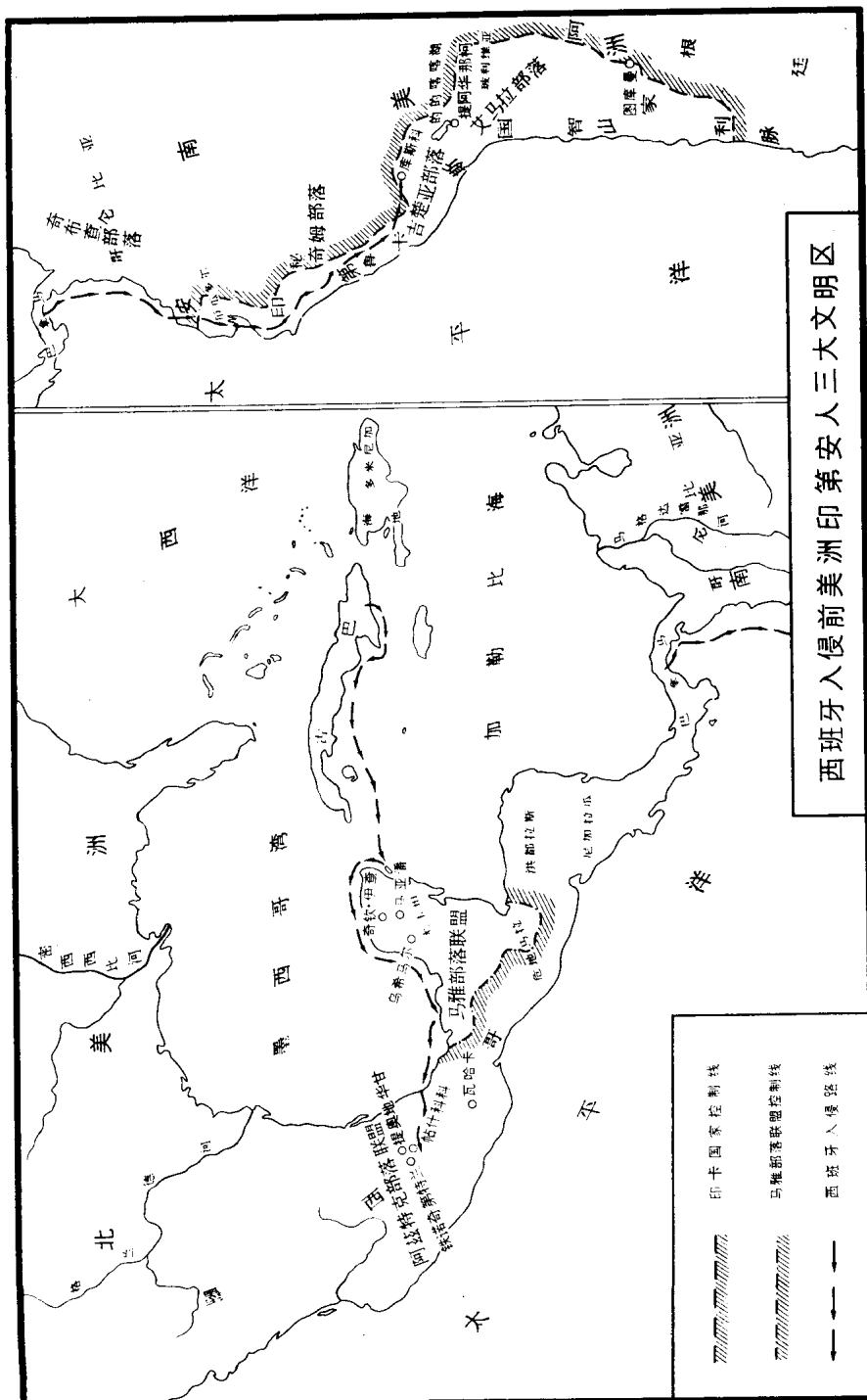
玄奘西行路线 (627-645年)








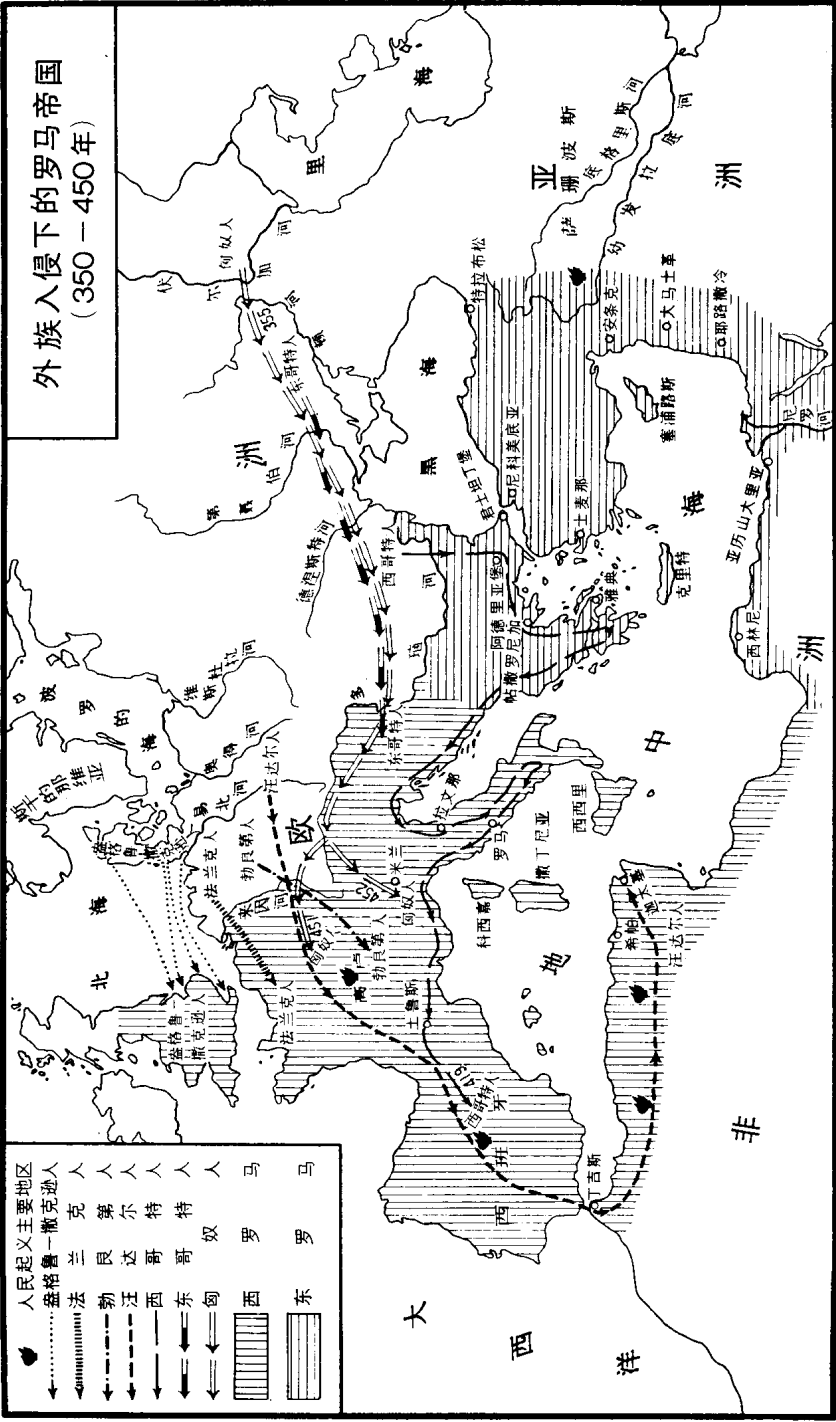
十三世纪末的亚洲



西班牙入侵前美洲印第安人三大文明区

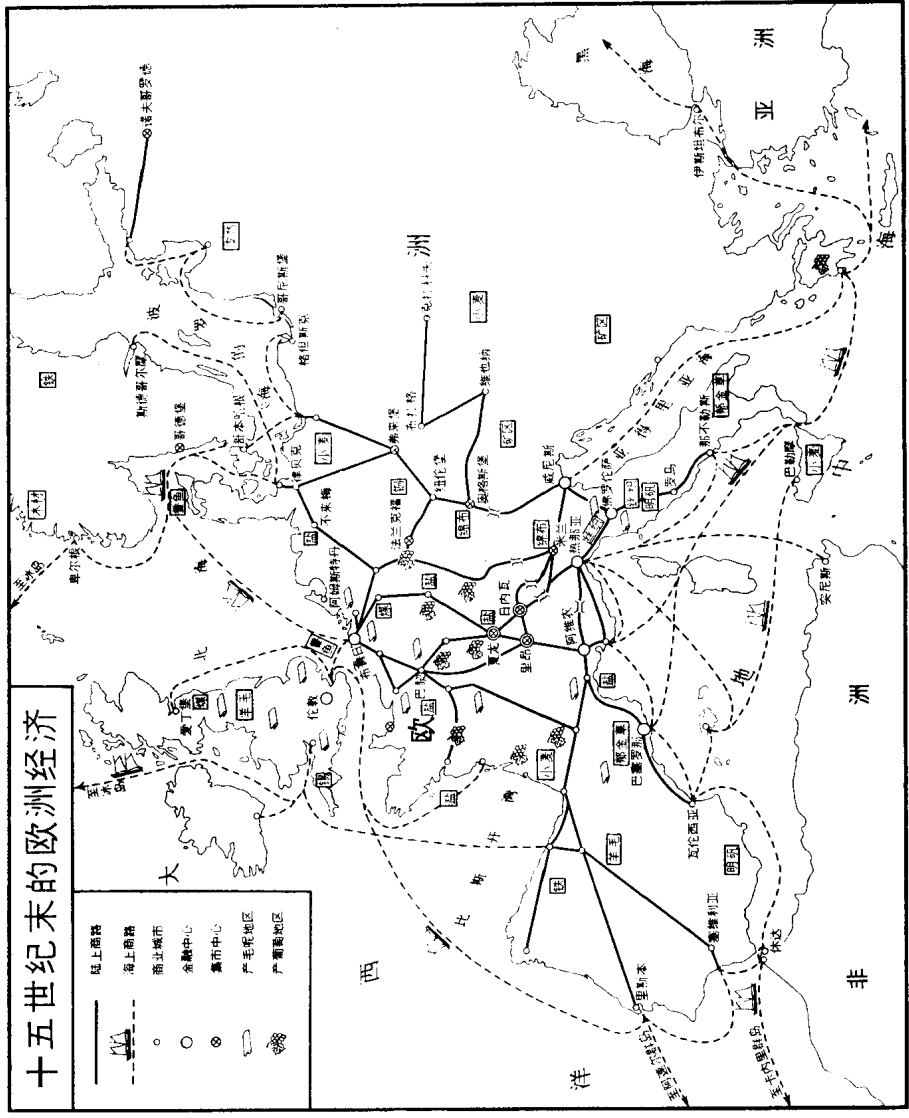


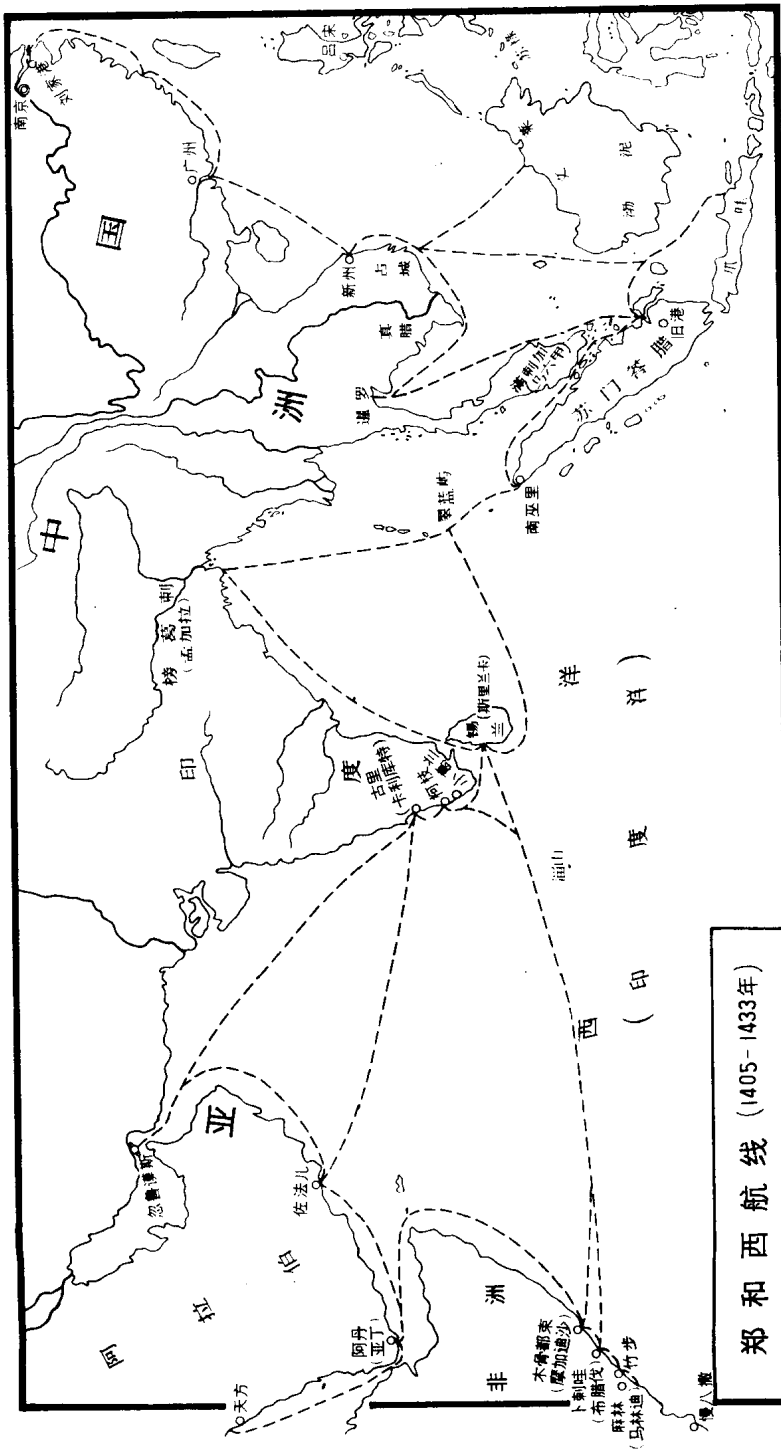
外族入侵下的罗马帝国 (350 - 450年)



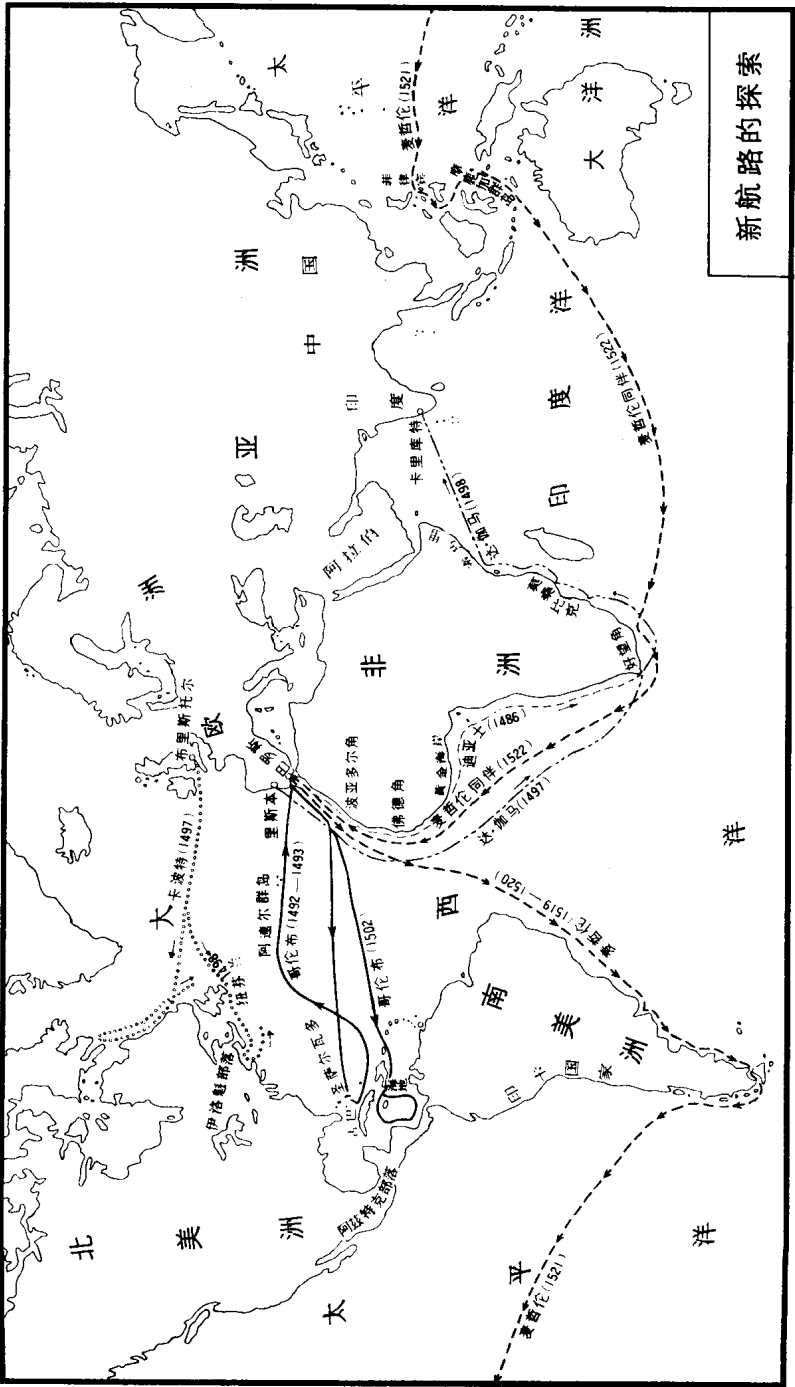
十五世纪末的欧洲经济

- 陆上商路
- - - 海上商路
- 商业城市
- 金融中心
- ⊙ 集市中心
- ◻ 羊毛产区
- ◻ 葡萄酒产区



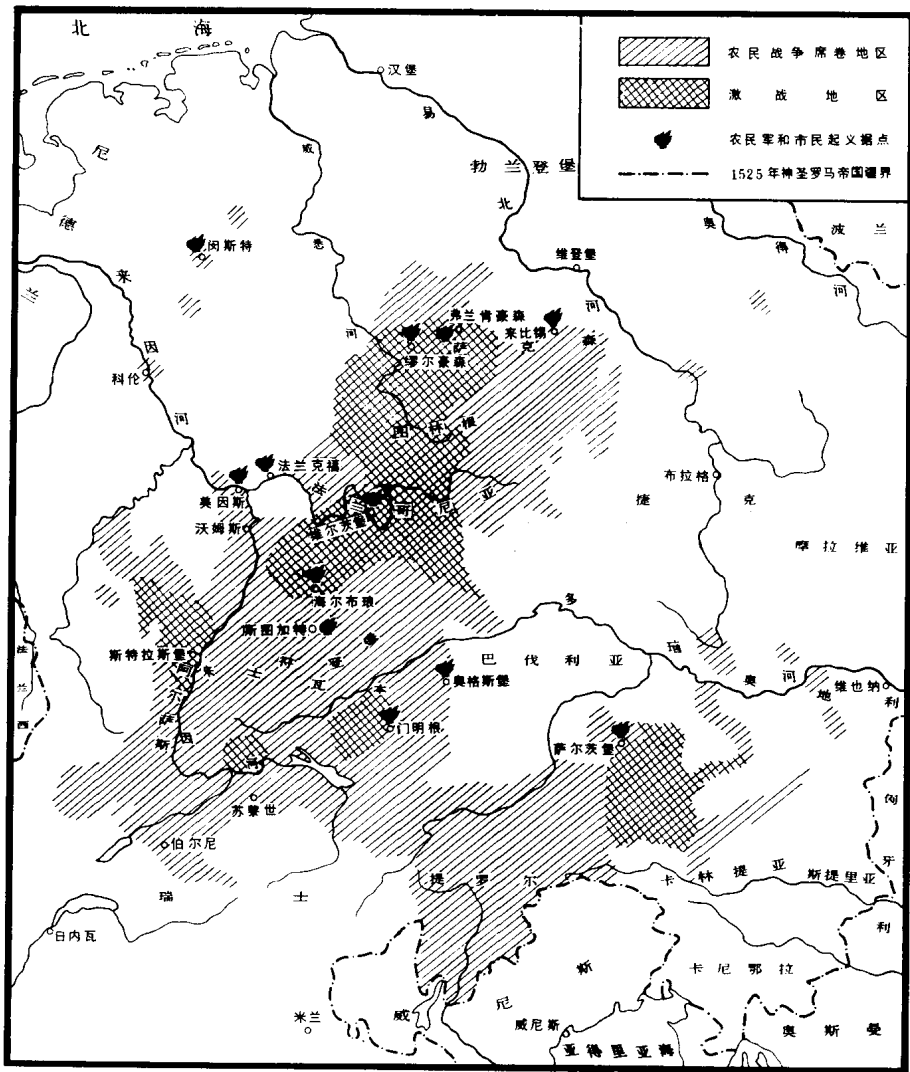


郑和西航线 (1405-1433年)

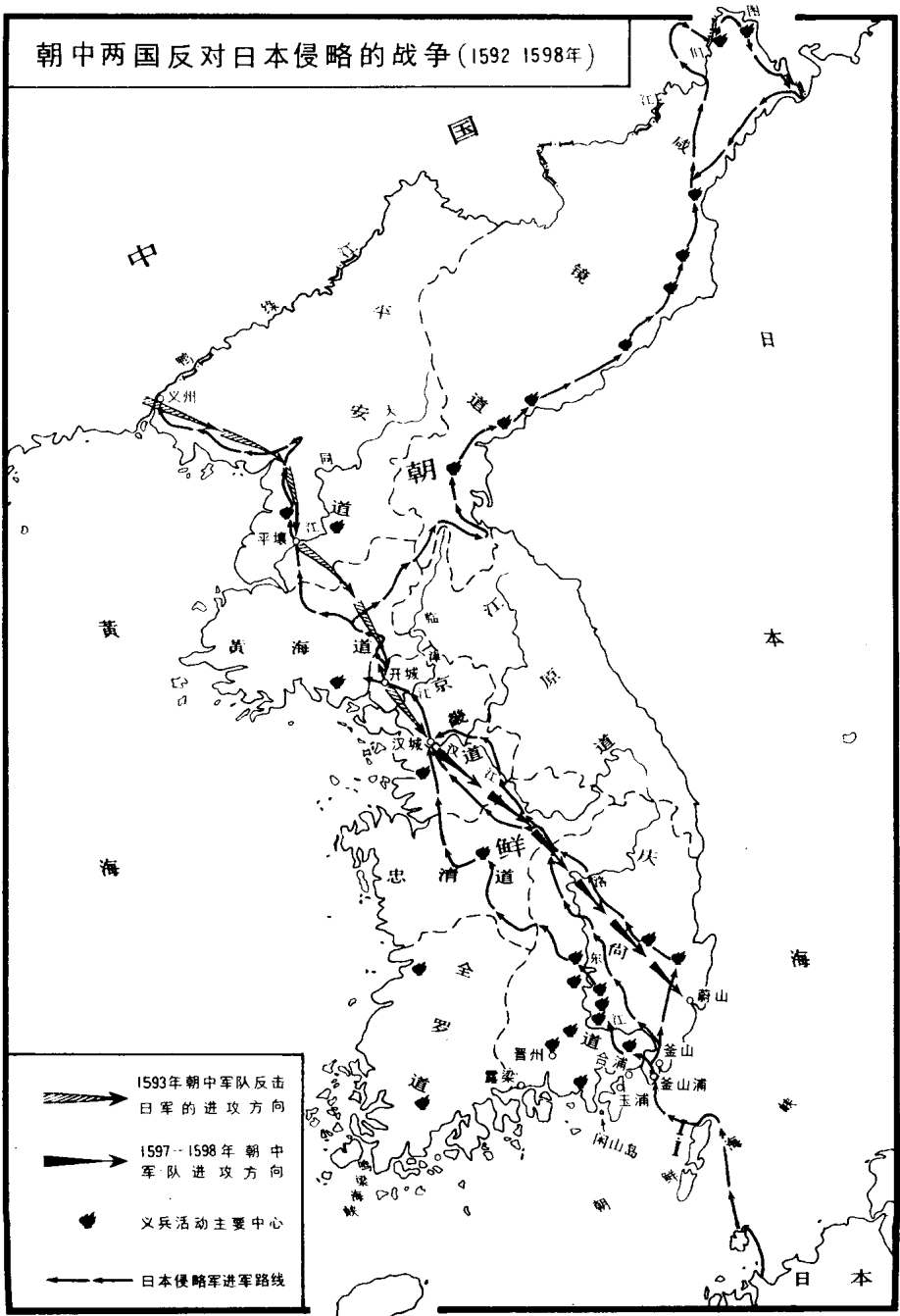






新航路的探索

德国农民战争








朝中两国反对日本侵略的战争 (1592-1598年)

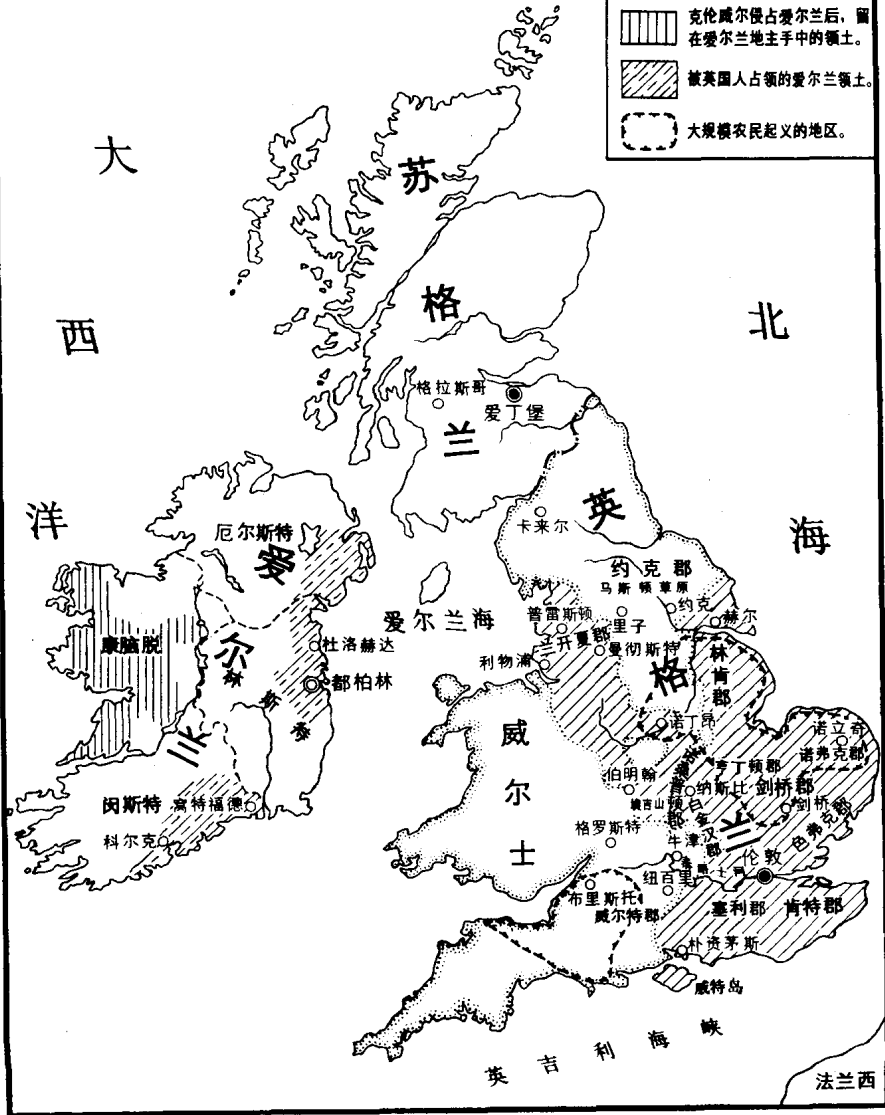


-  1593年朝中军队反击日军的进攻方向
-  1597-1598年朝中军队进攻方向
-  义兵活动主要中心
-  日本侵略军进军路线

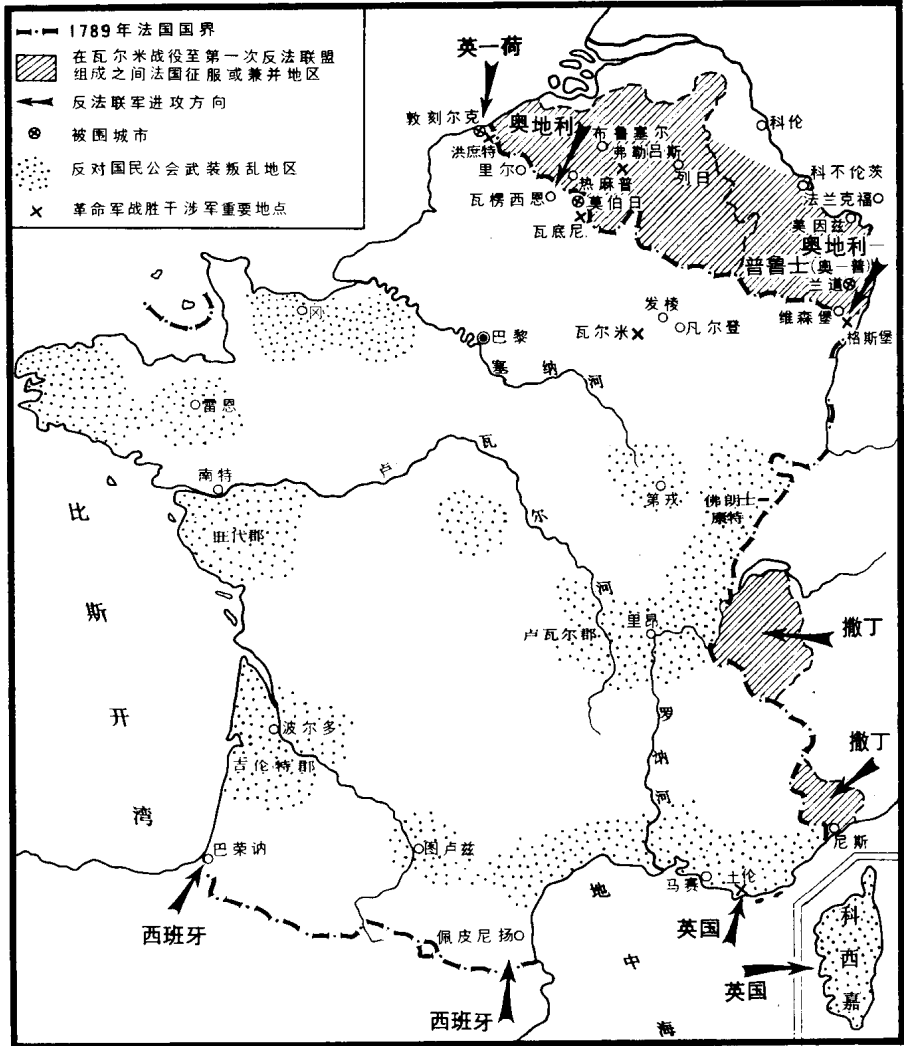
近代部分

十七世纪英国资产阶级革命

-  国会控制的地区 (到1643年底止)。
-  国王控制的地区 (到1643年底止)。
-  克伦威尔侵占爱尔兰后, 留在爱尔兰地主手中的领土。
-  被英国人占领的爱尔兰领土。
-  大规模农民起义的地区。

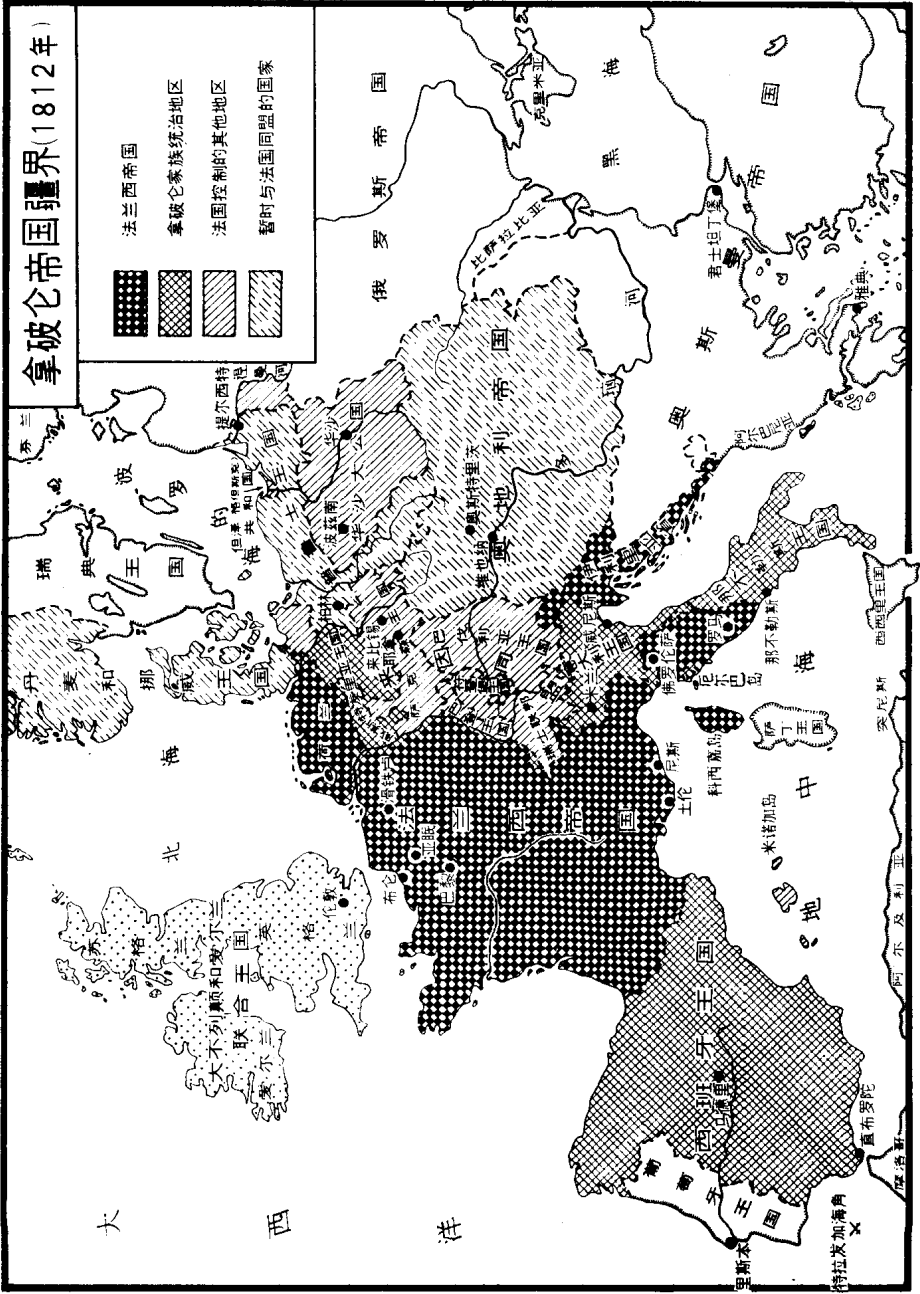


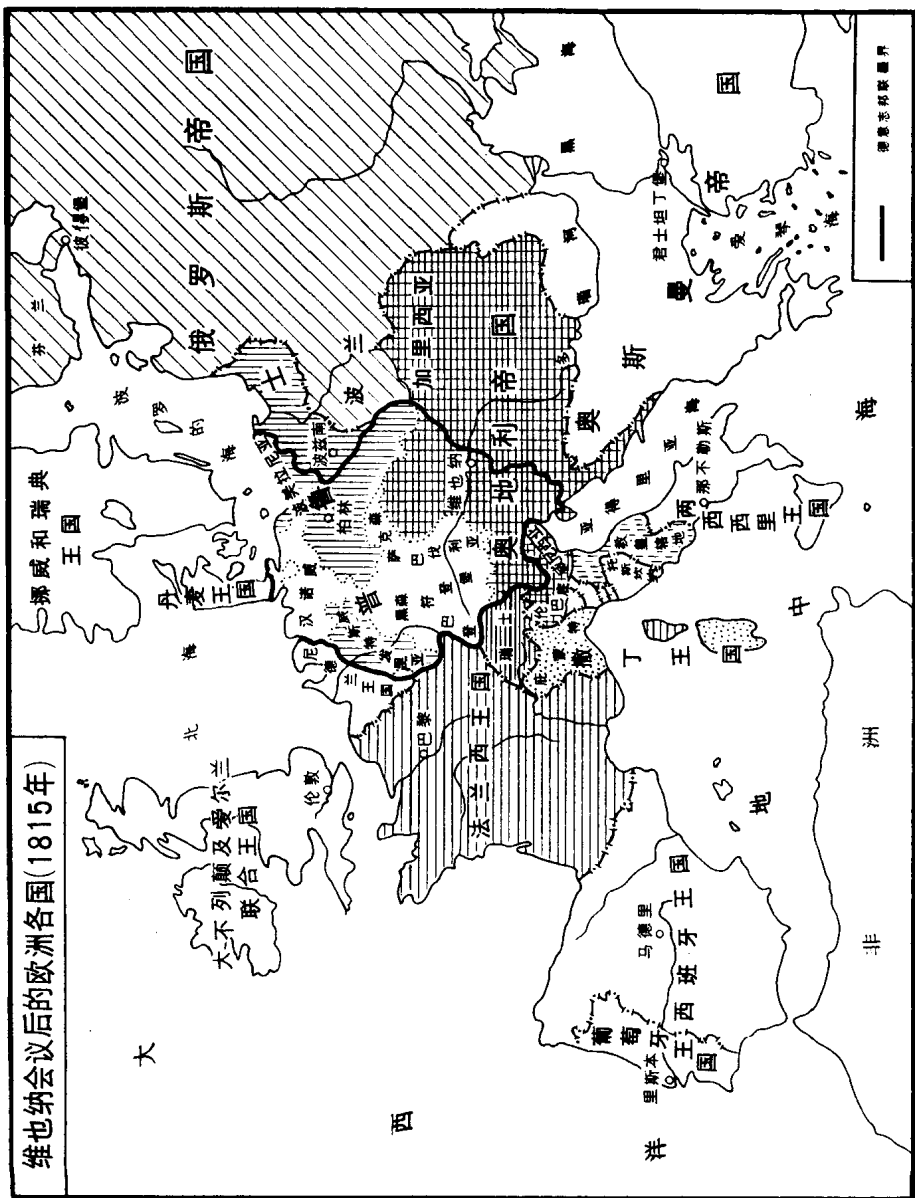
1792 — 1794 年的法国



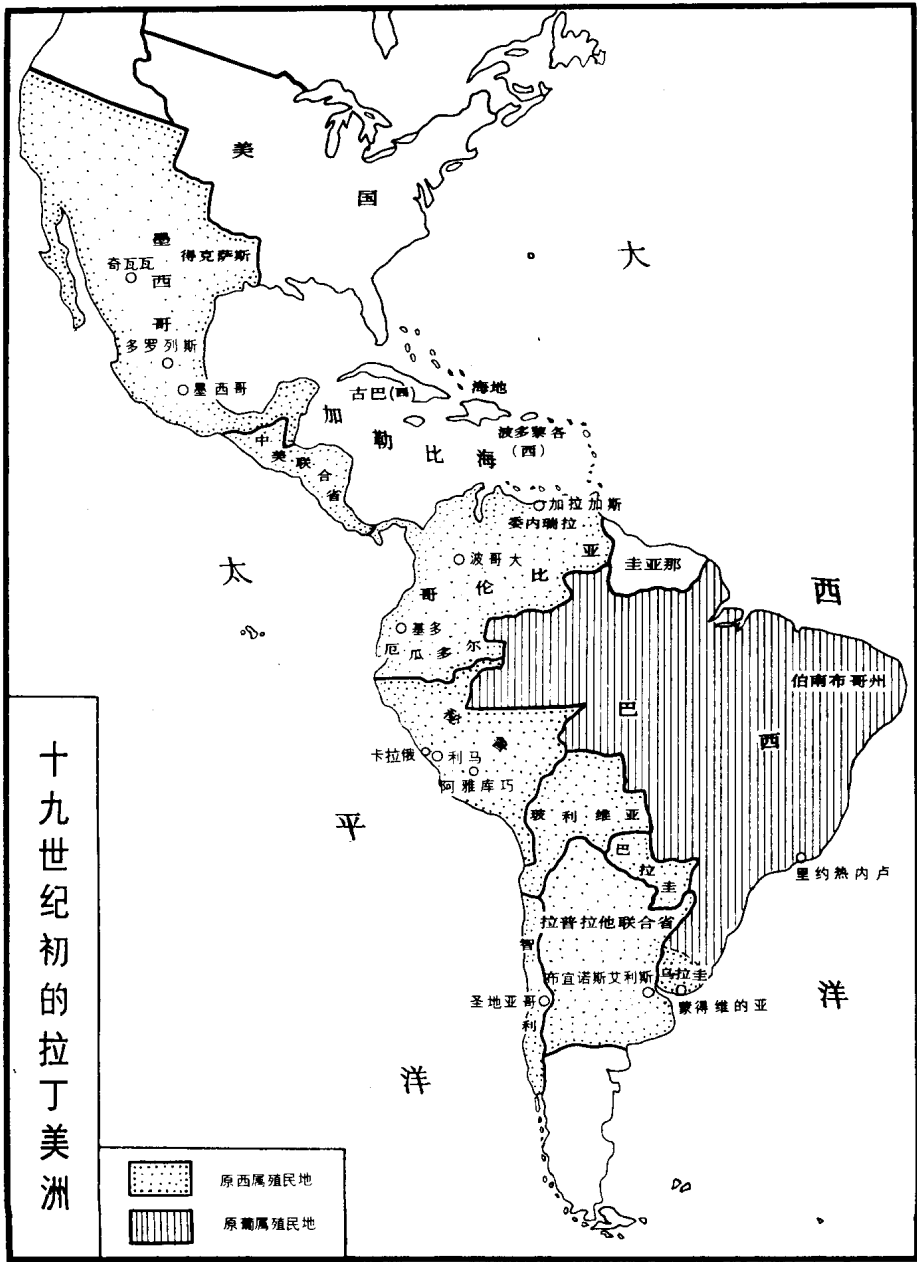
拿破仑帝国疆界(1812年)

- 法兰西帝国
- ▣ 拿破仑家族统治地区
- ▤ 法国控制的其他地区
- ▥ 暂时与法国同盟的国家

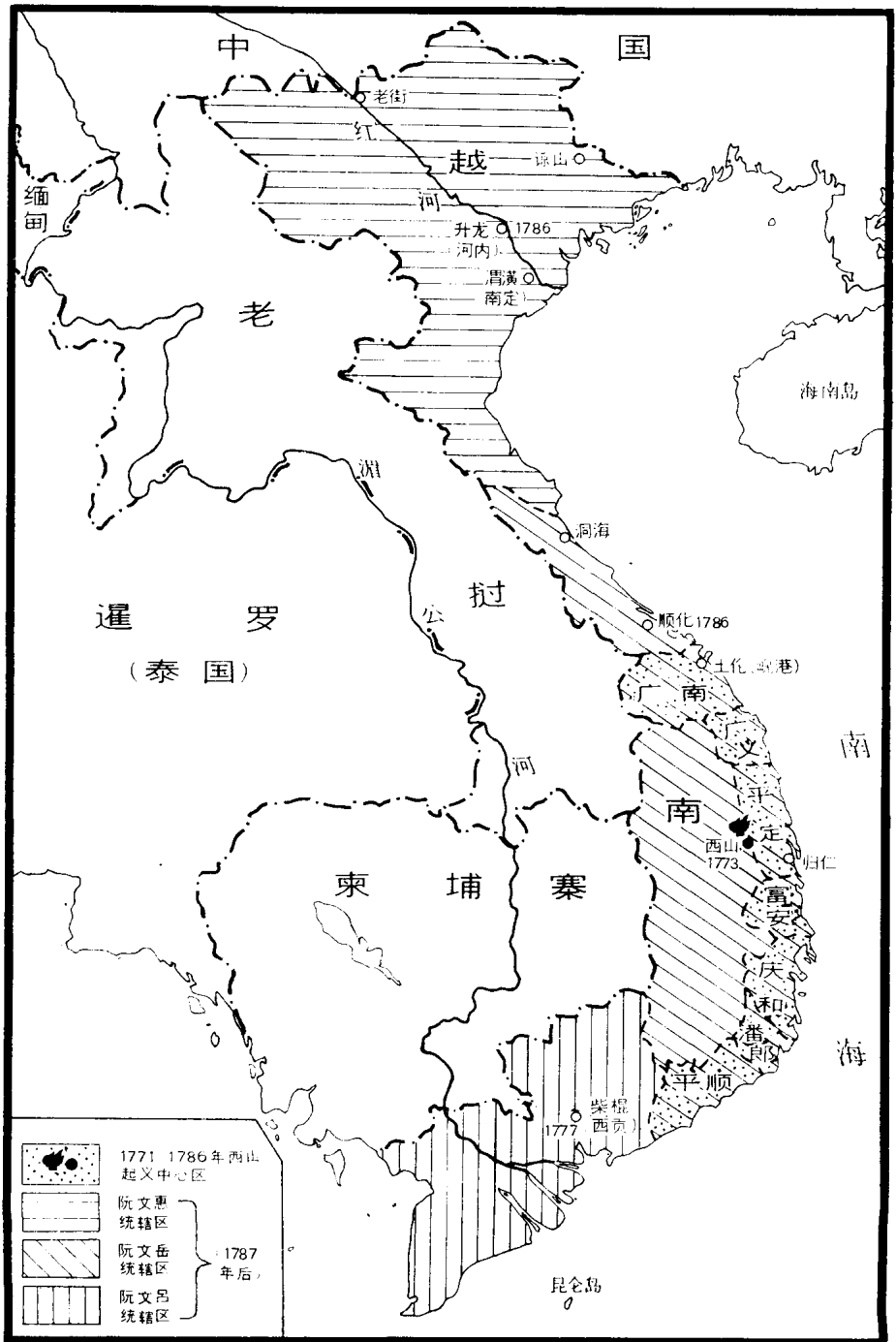


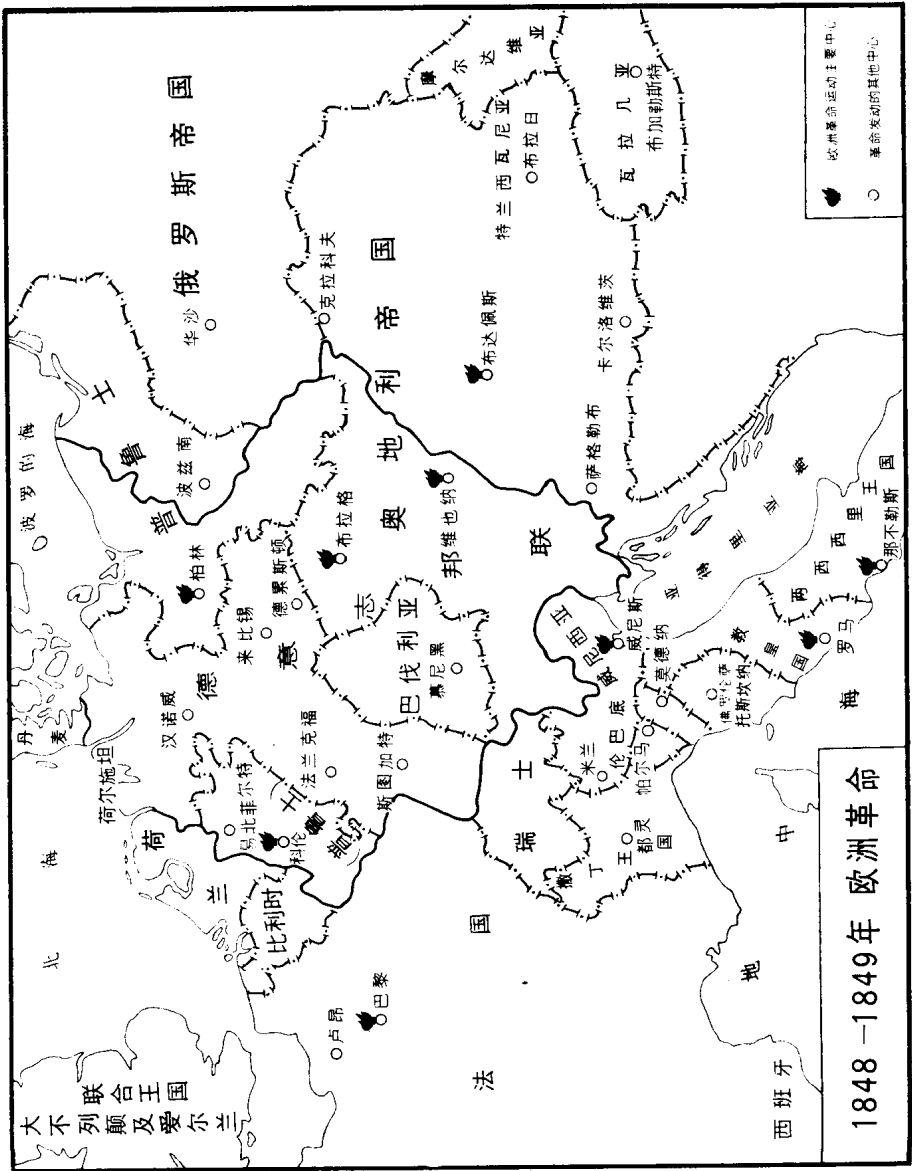


维也纳会议后的欧洲各国(1815年)

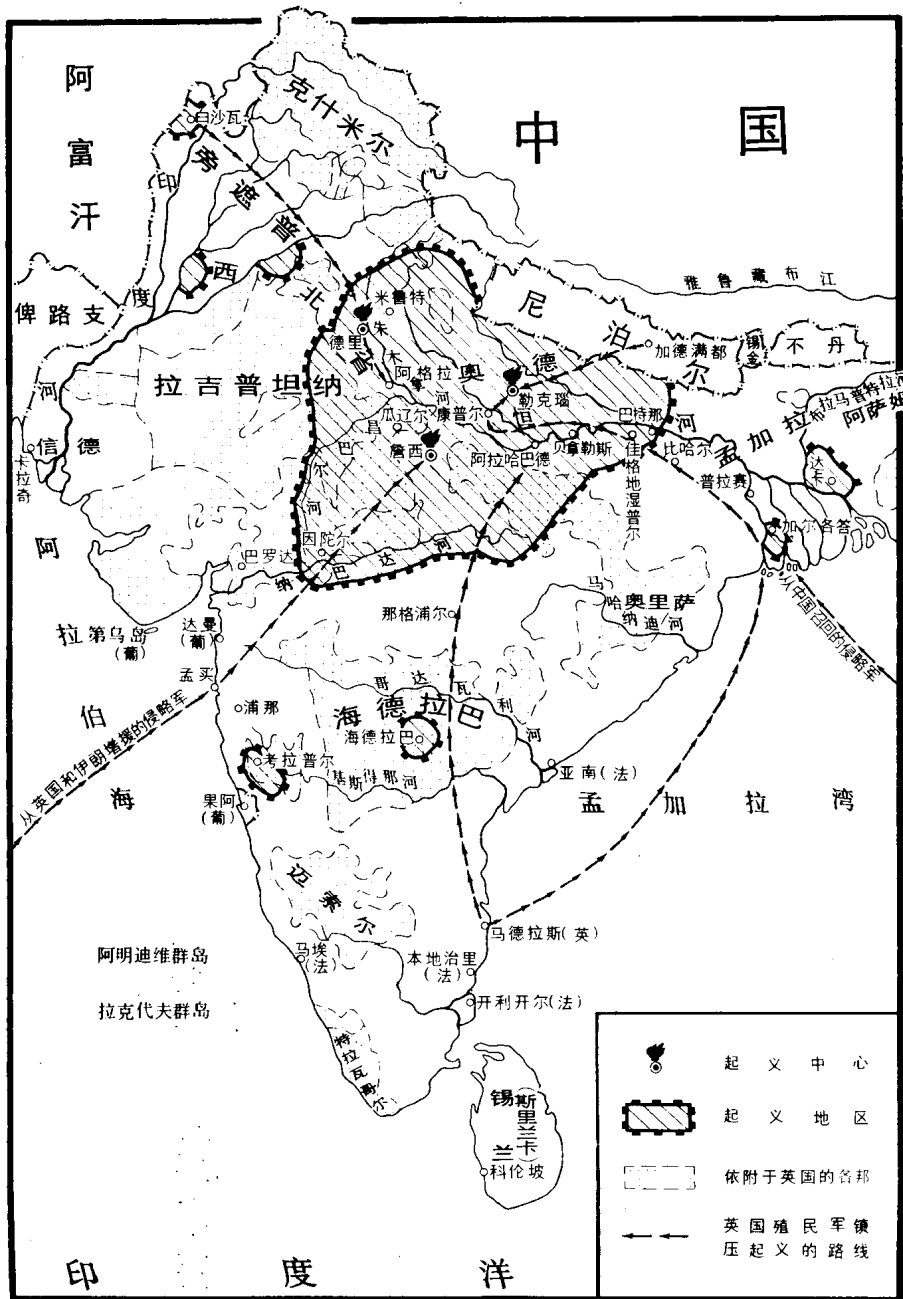


西山起义(1771-1802年)

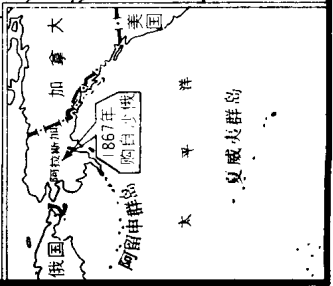
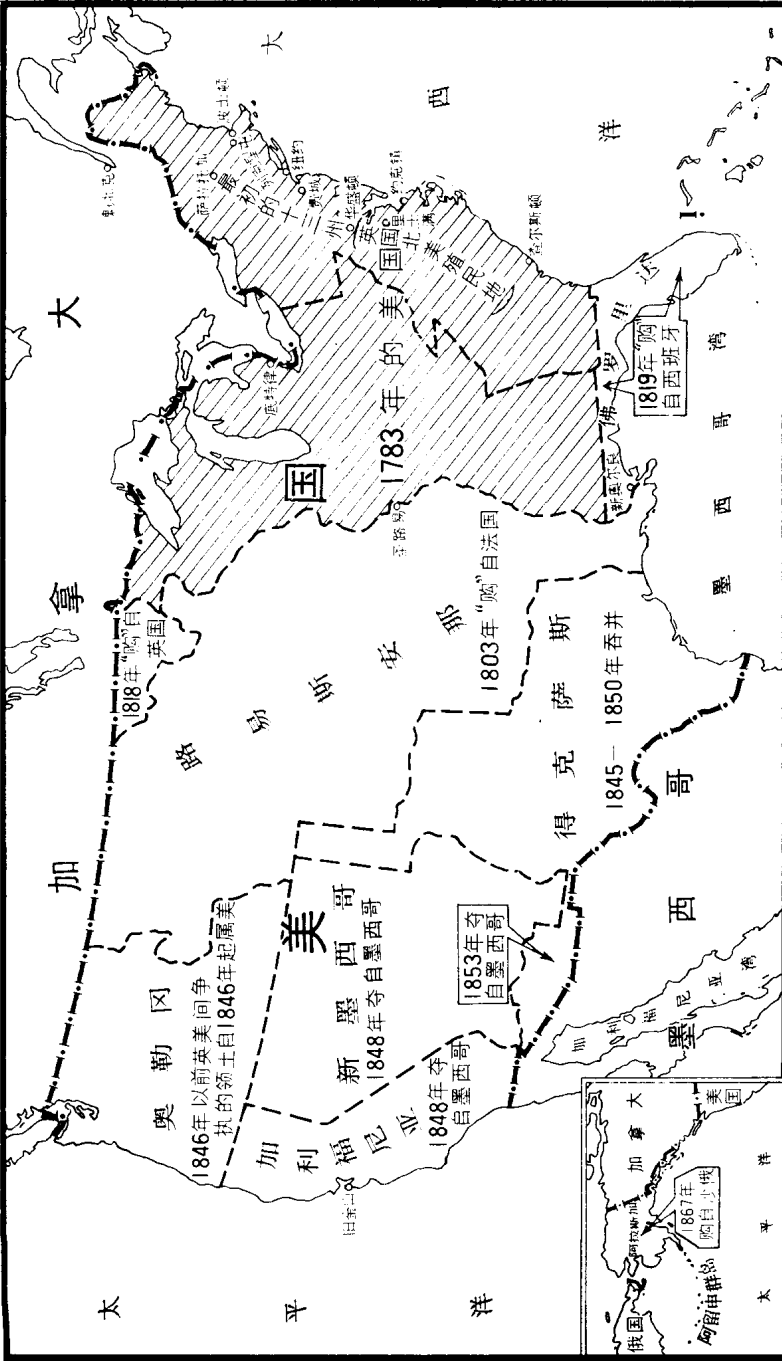




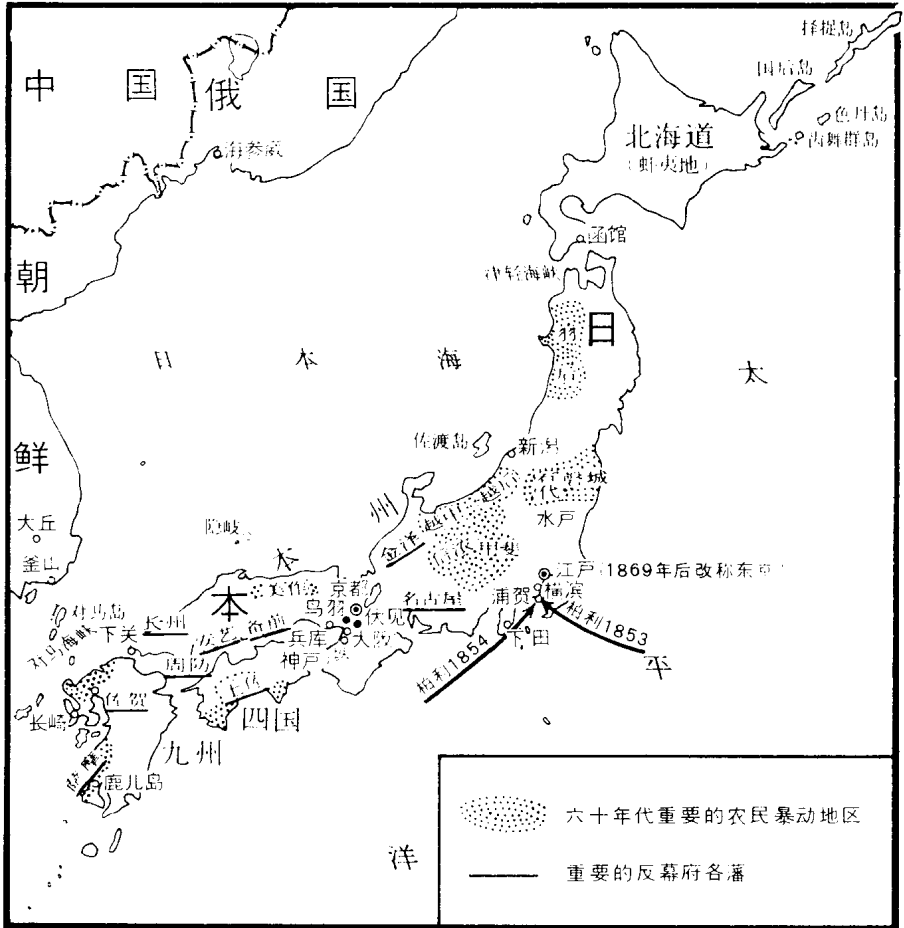
印度民族大起义(1857—1859年)



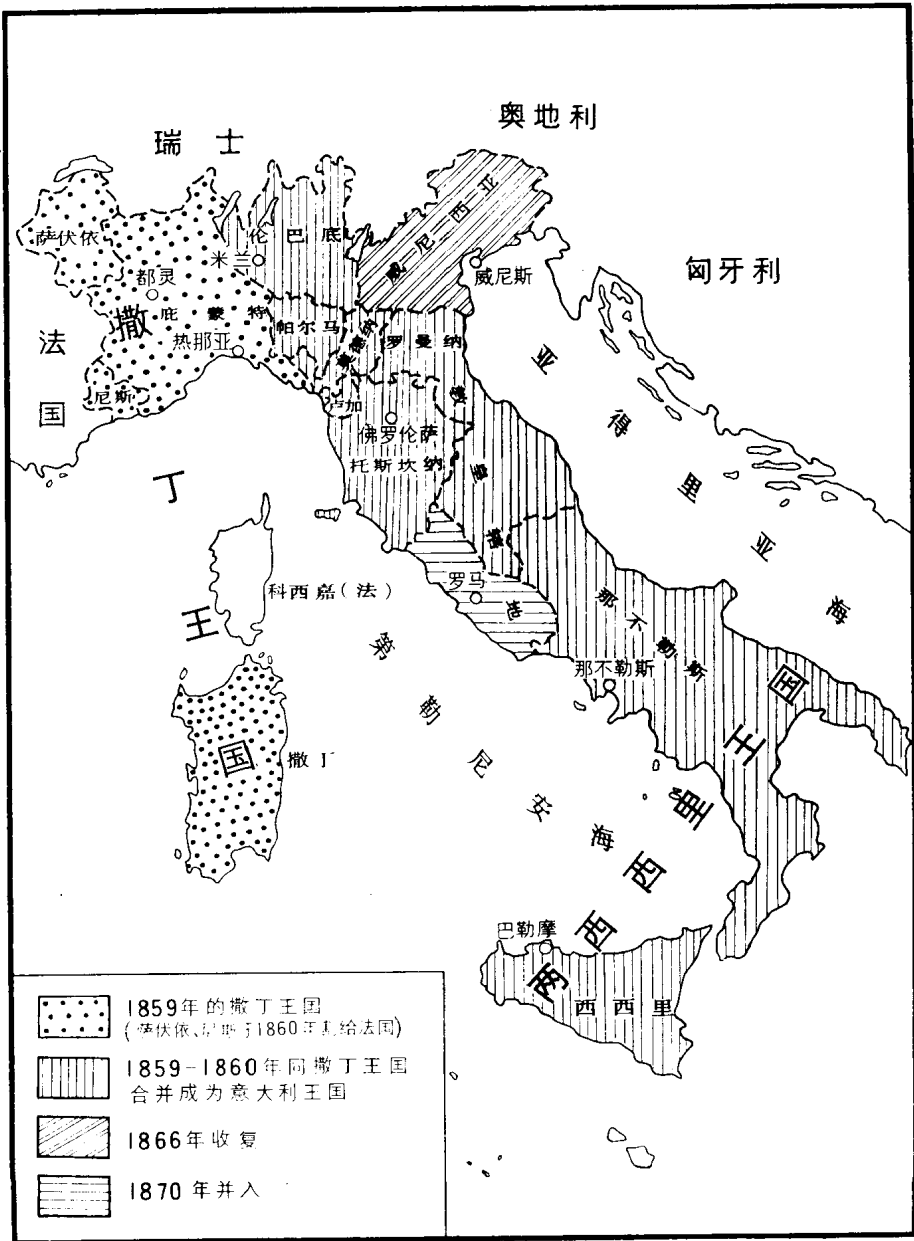
十八世纪末到十九世纪六十年代的美国领土扩张



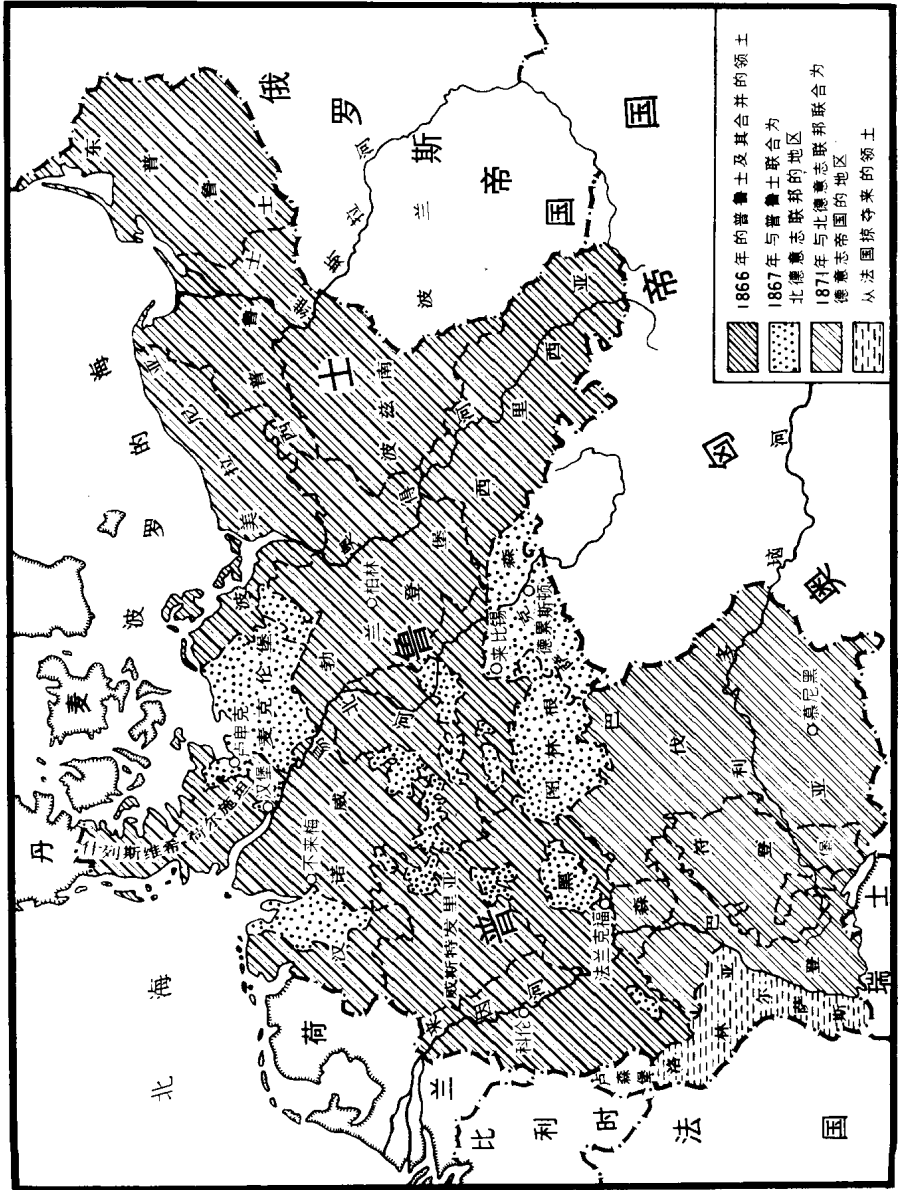
十九世纪中叶日本的反幕府斗争



意大利的统一

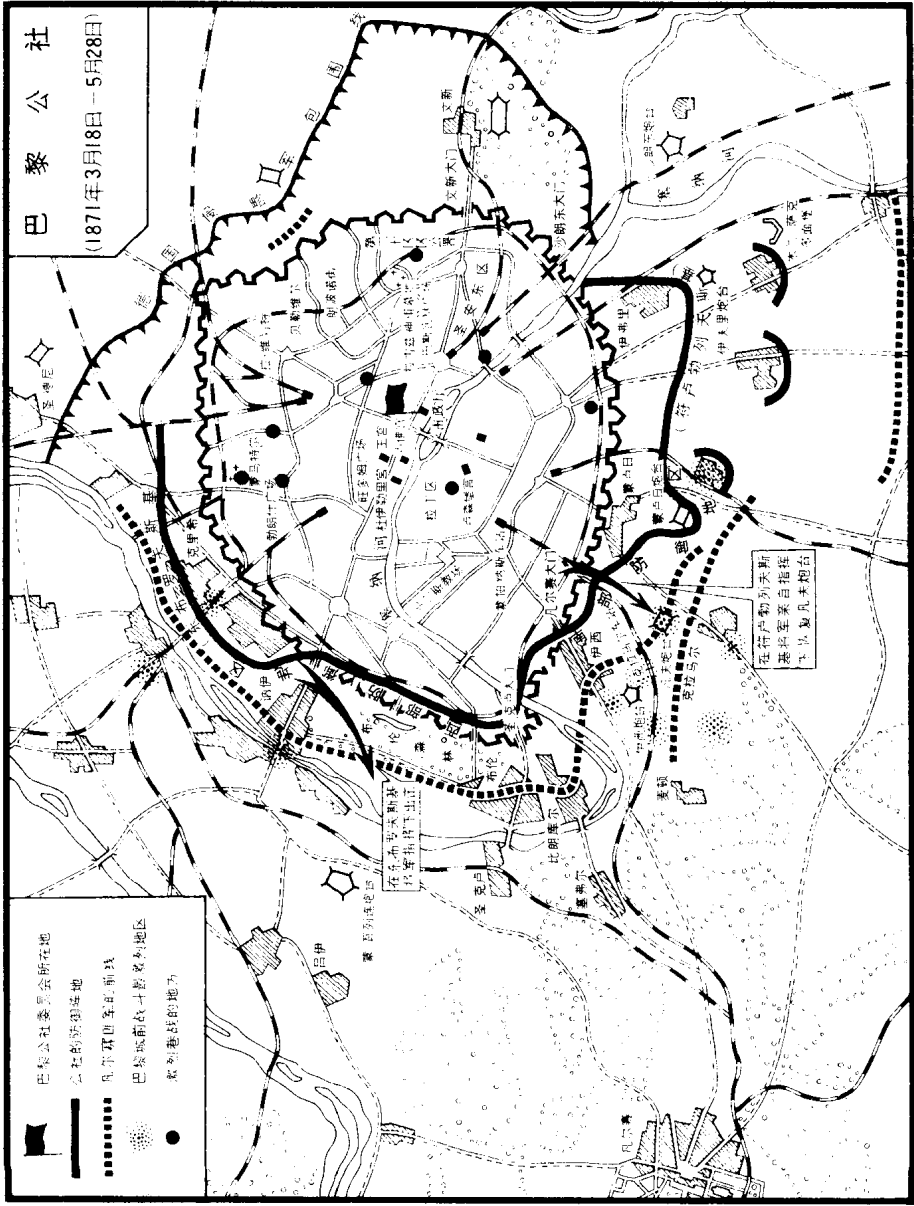


德意志的统一



巴黎公社

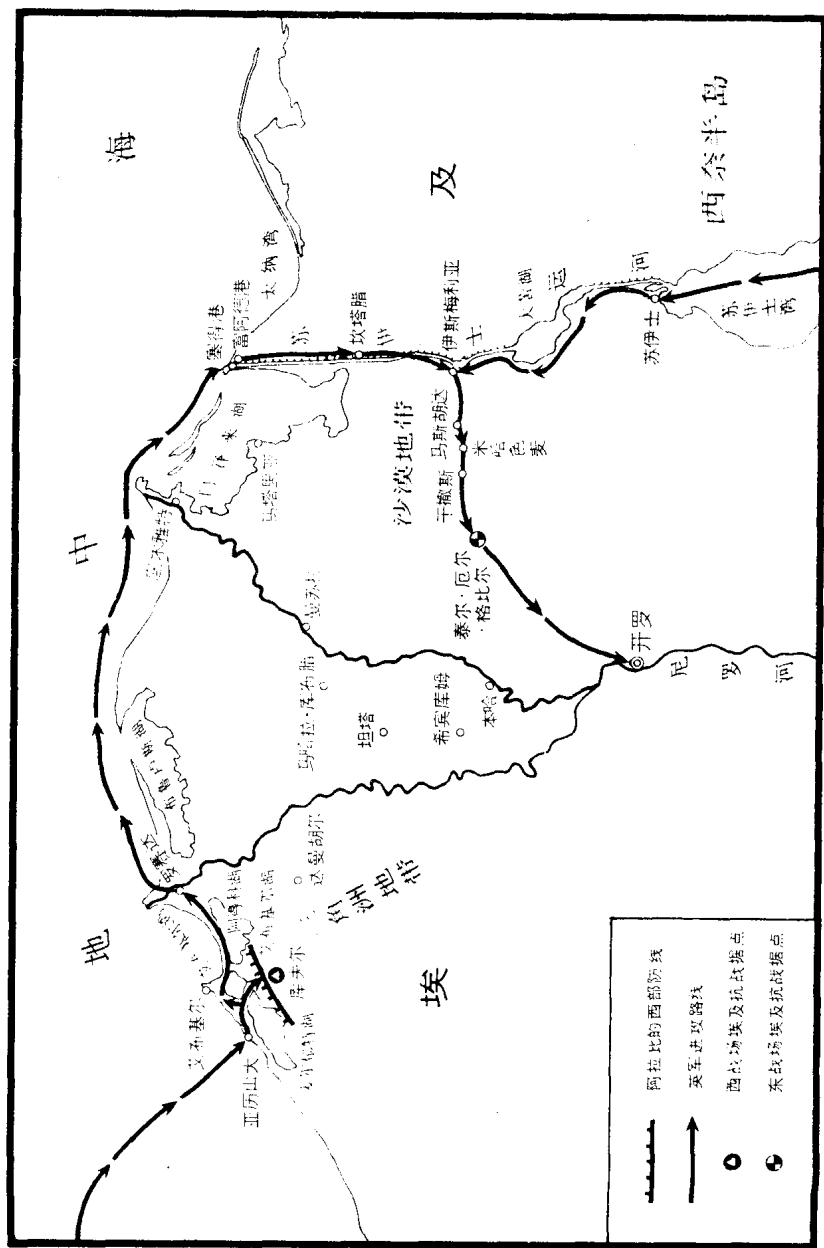
(1871年3月18日 - 5月28日)



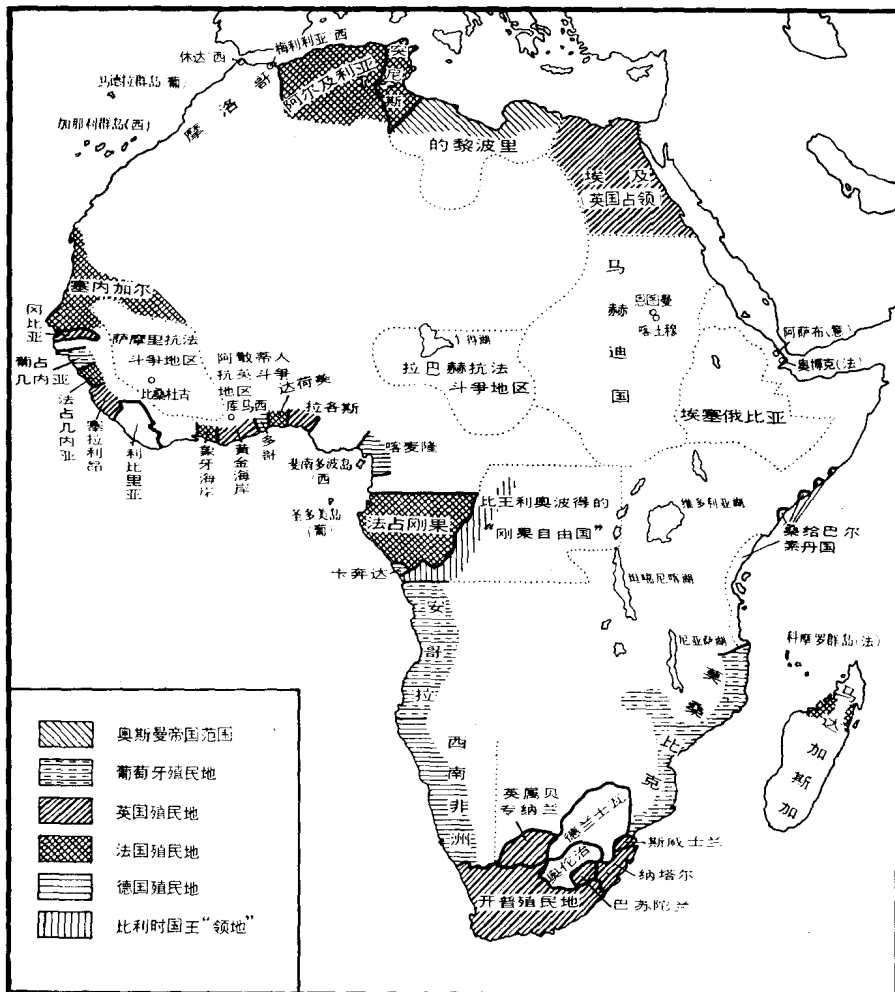
- 巴黎公社委员会所在地
- 公社的领土
- 凡尔赛军队的战线
- 巴黎城前夜一半夜攻占的地区
- 重新占领的地方

在凡尔赛军队和巴黎公社之间
 凡尔赛军队和巴黎公社
 巴黎公社和凡尔赛军队

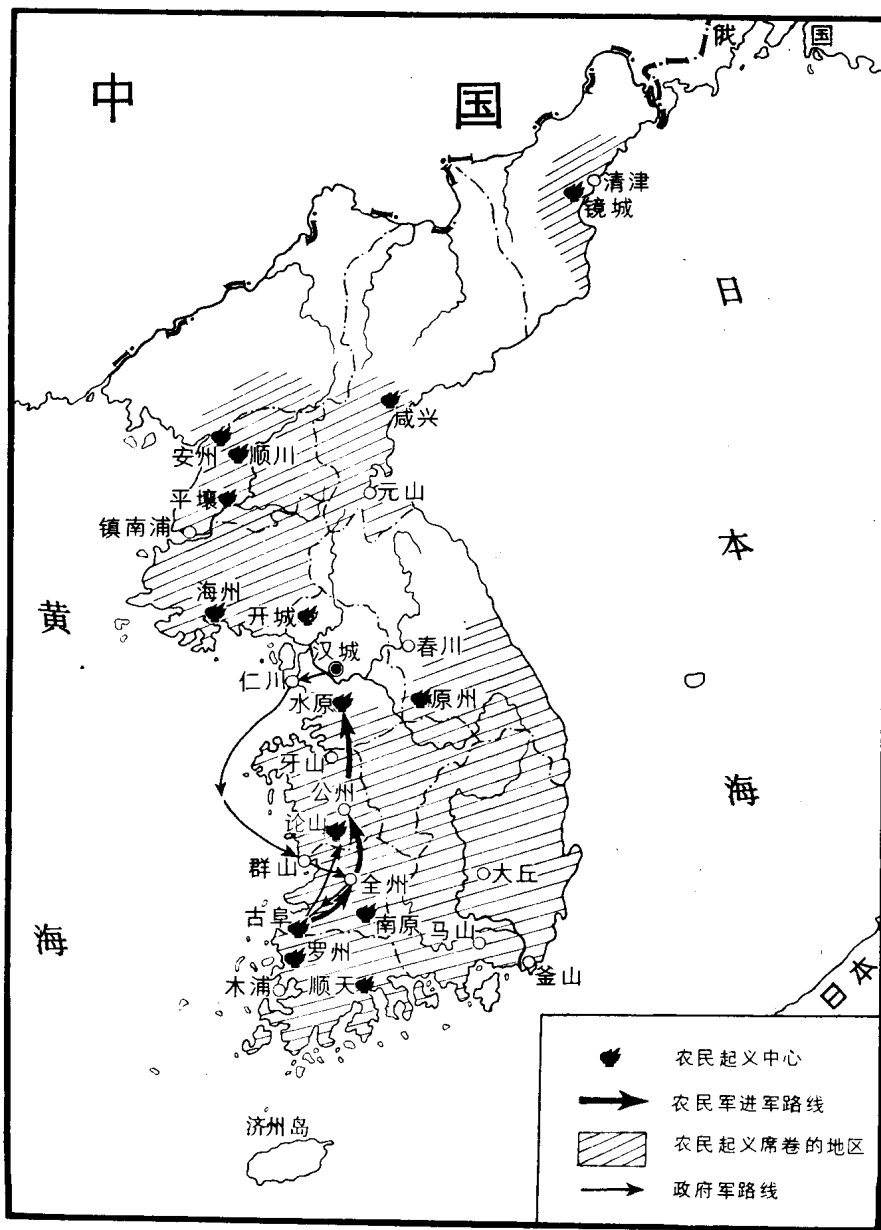
1882年英国武装进攻埃及和埃及军民抗战



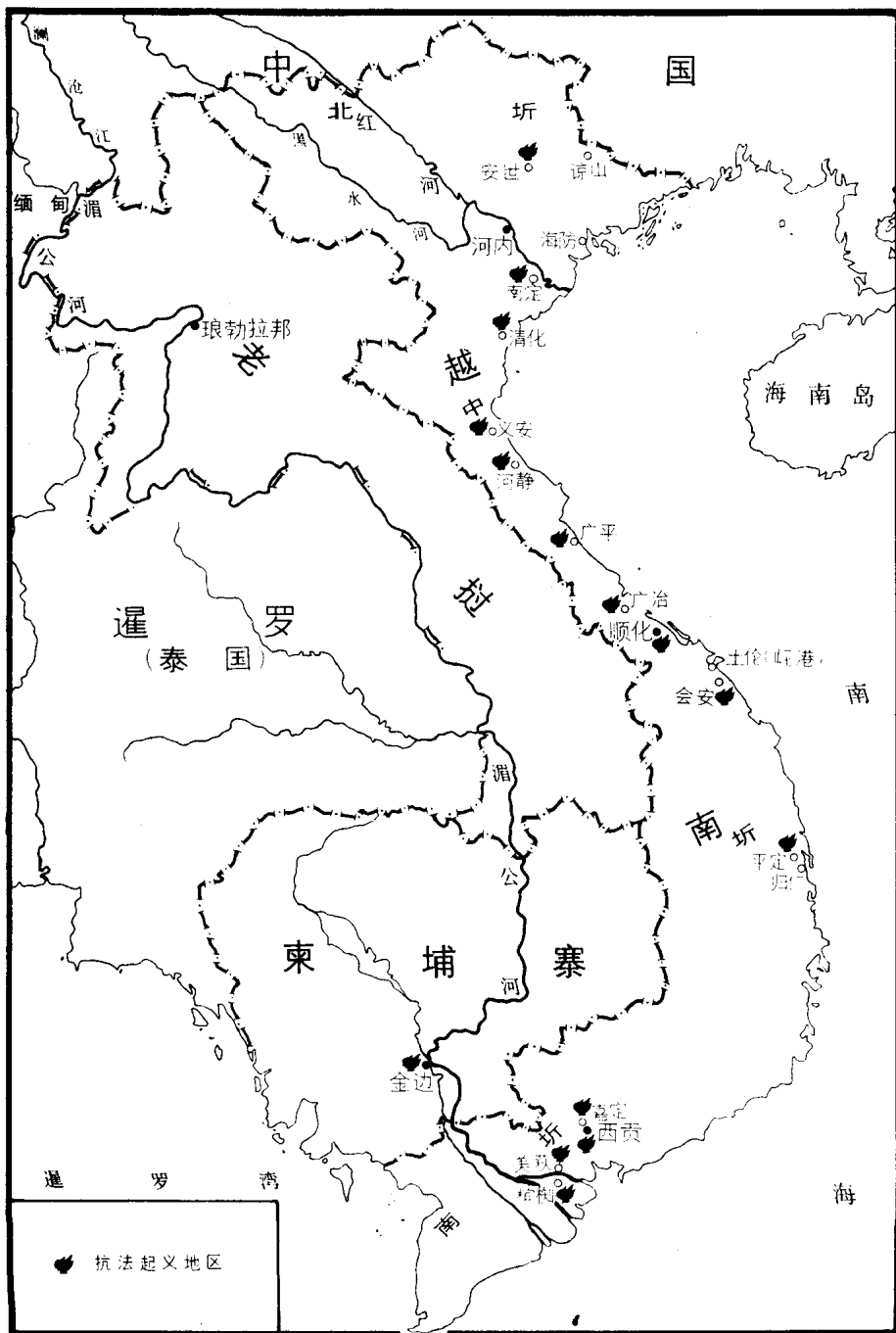
1885年帝国主义对非洲的占领



朝鲜农民战争(1894-1895年)

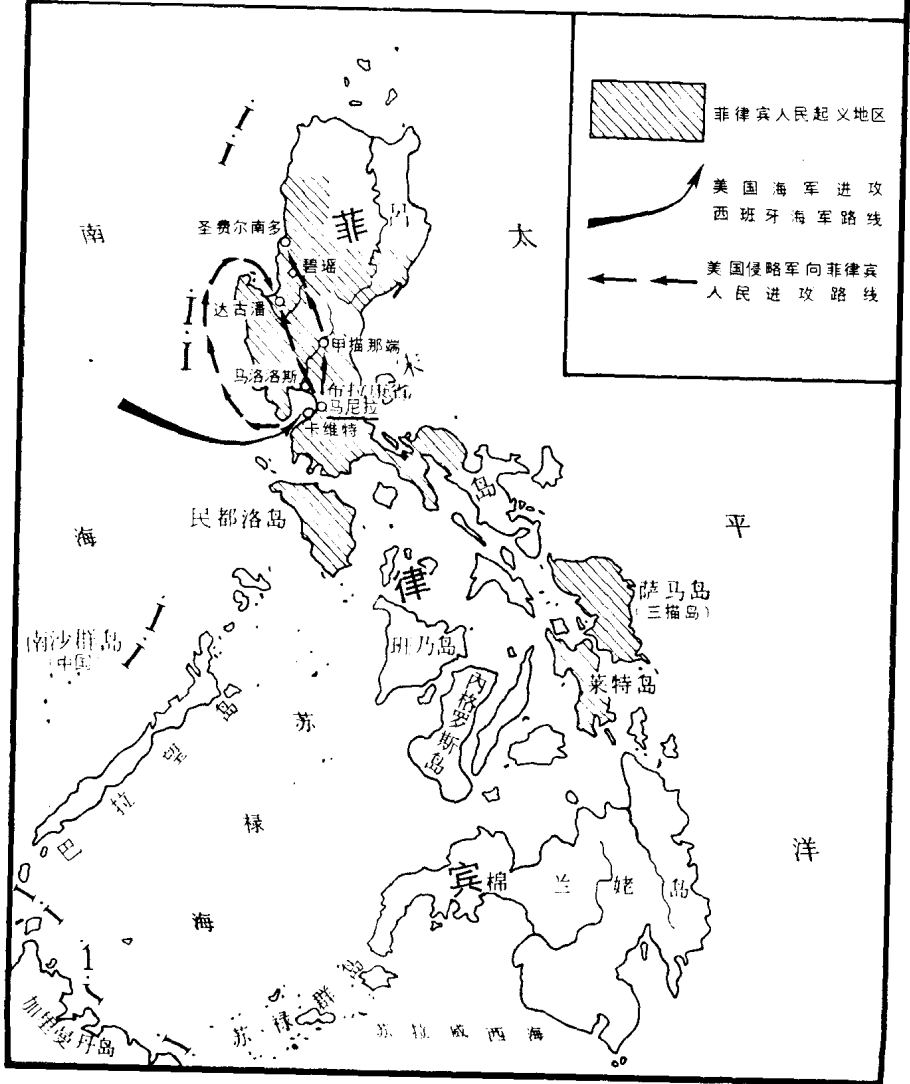


印度支那人民抗法斗争(十九世纪末到二十世纪初)

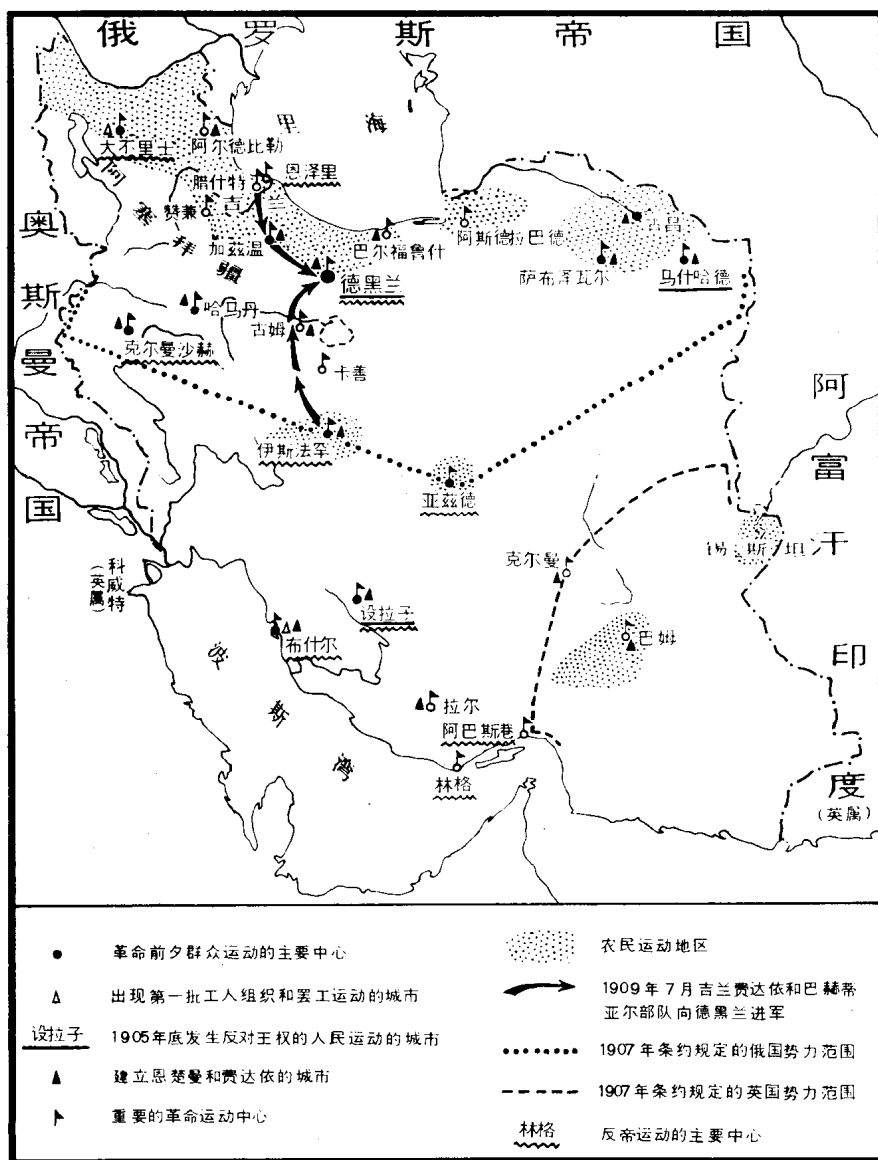


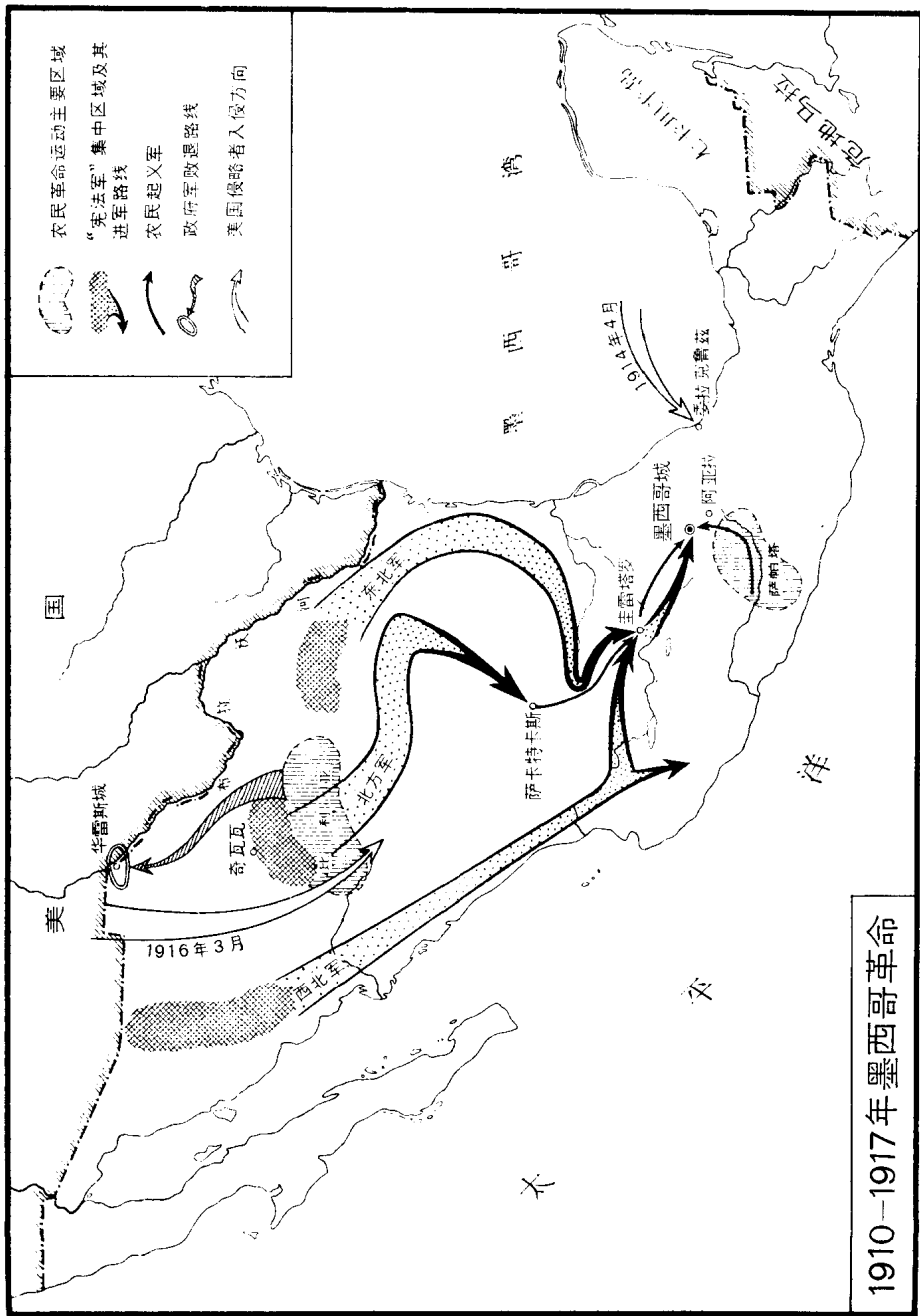
1898—1906 年的 菲 律 宾

(1898年前由西班牙占领,1898年后由美国占领)



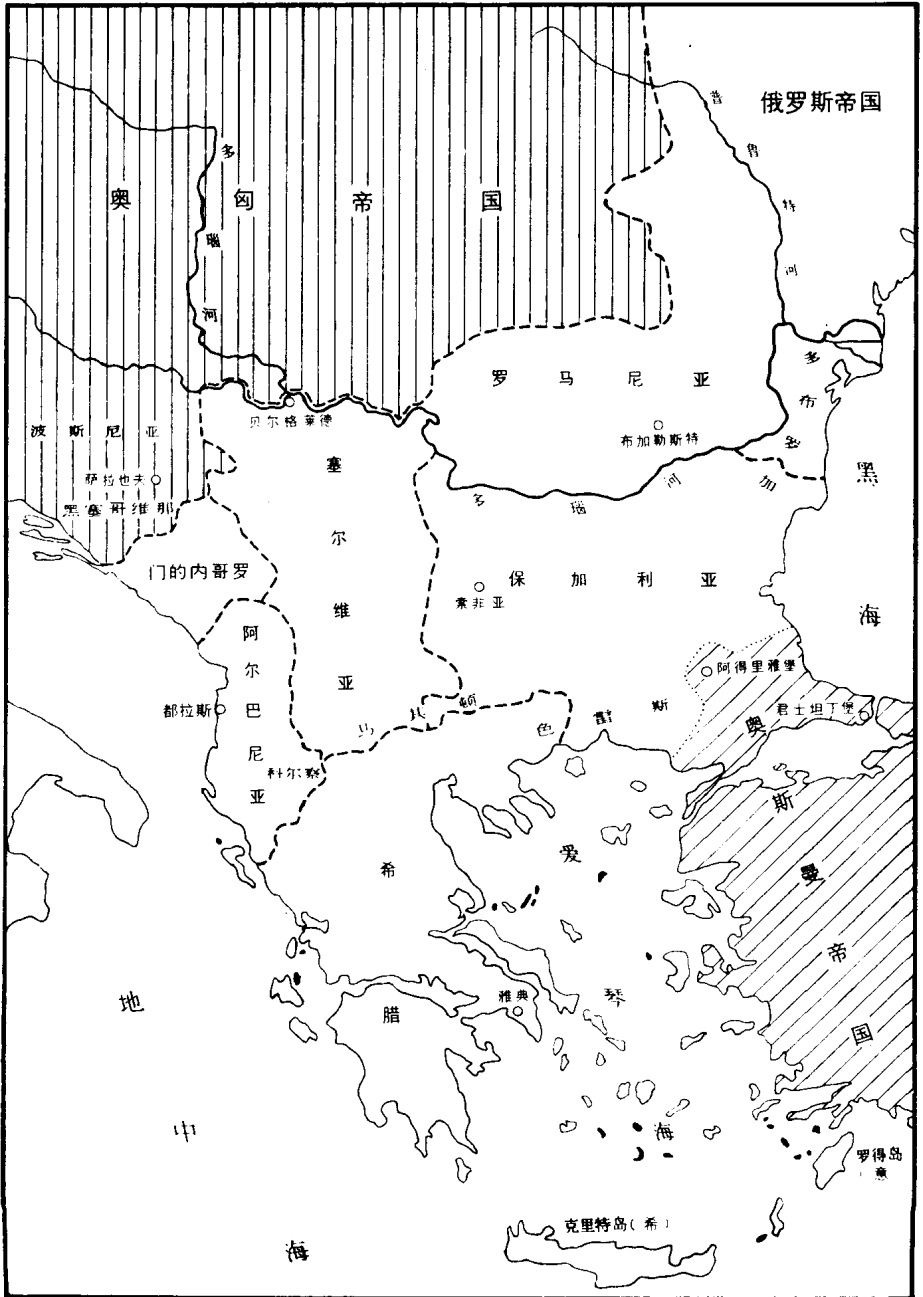
1905-1911年伊朗革命



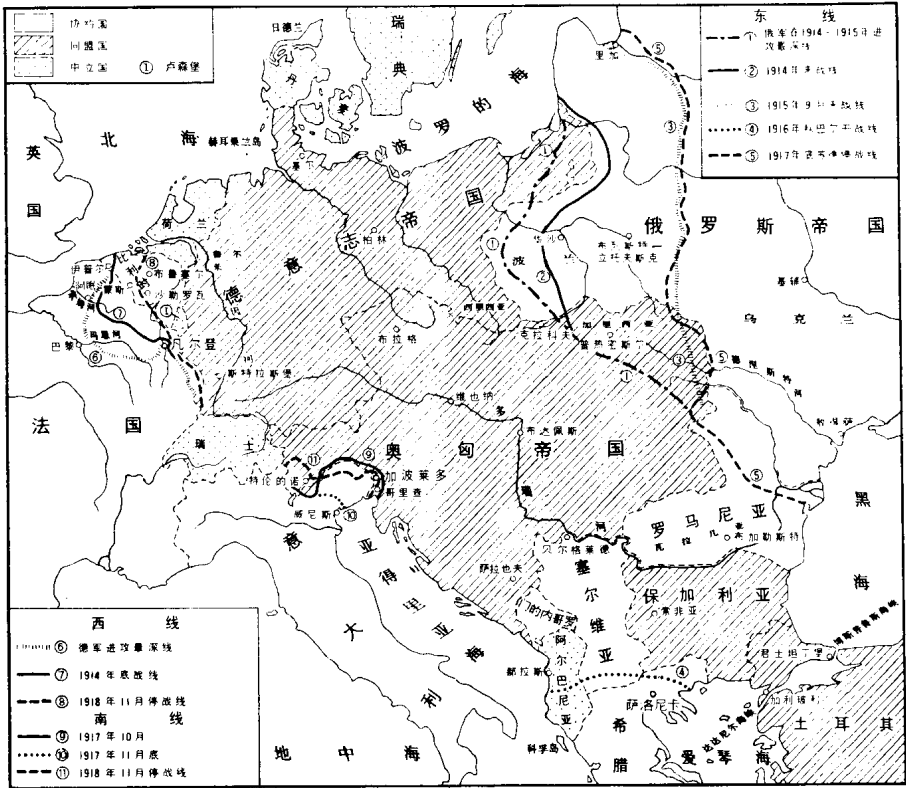


1910—1917年墨西哥革命

第一次世界大战前夕的巴尔干半岛



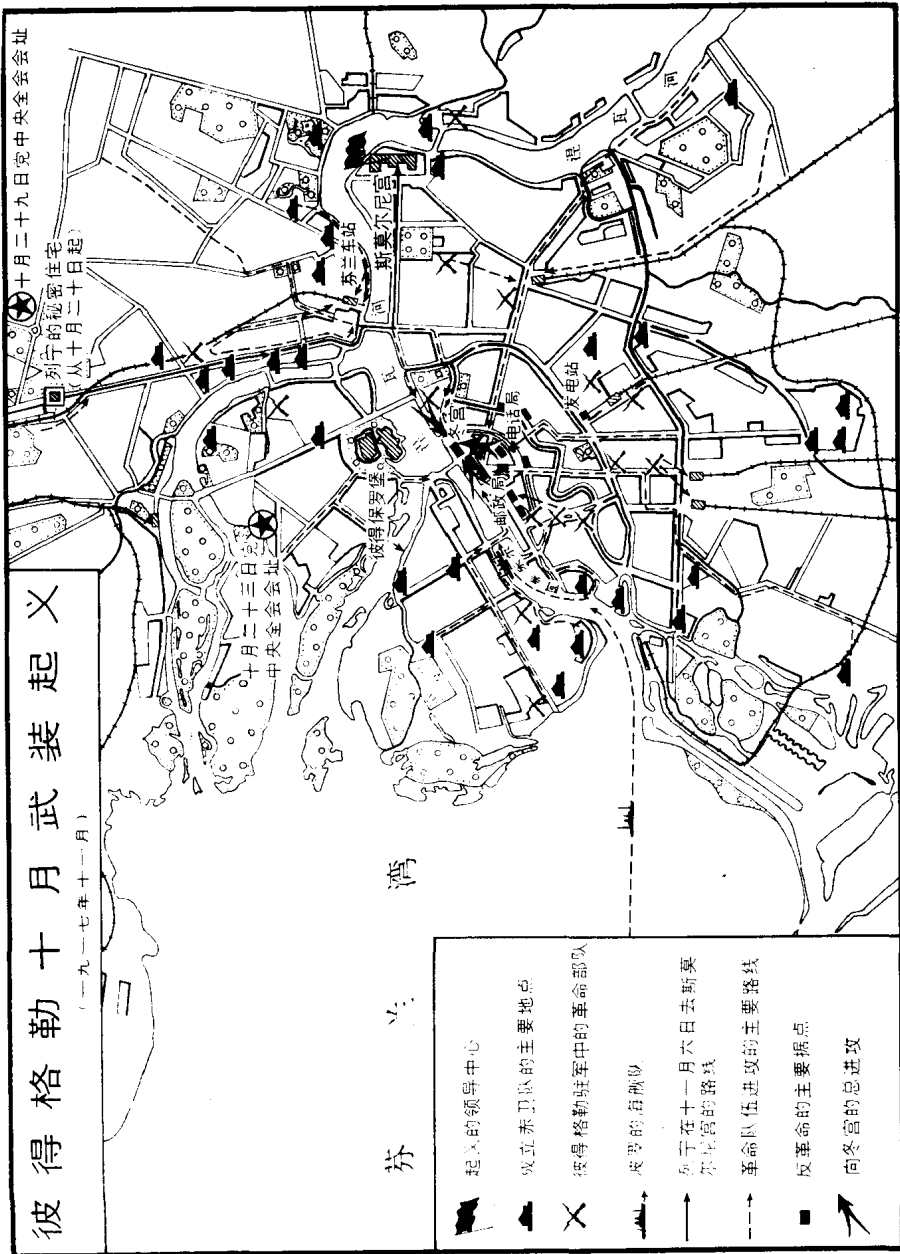
第一次世界大战











现代部分

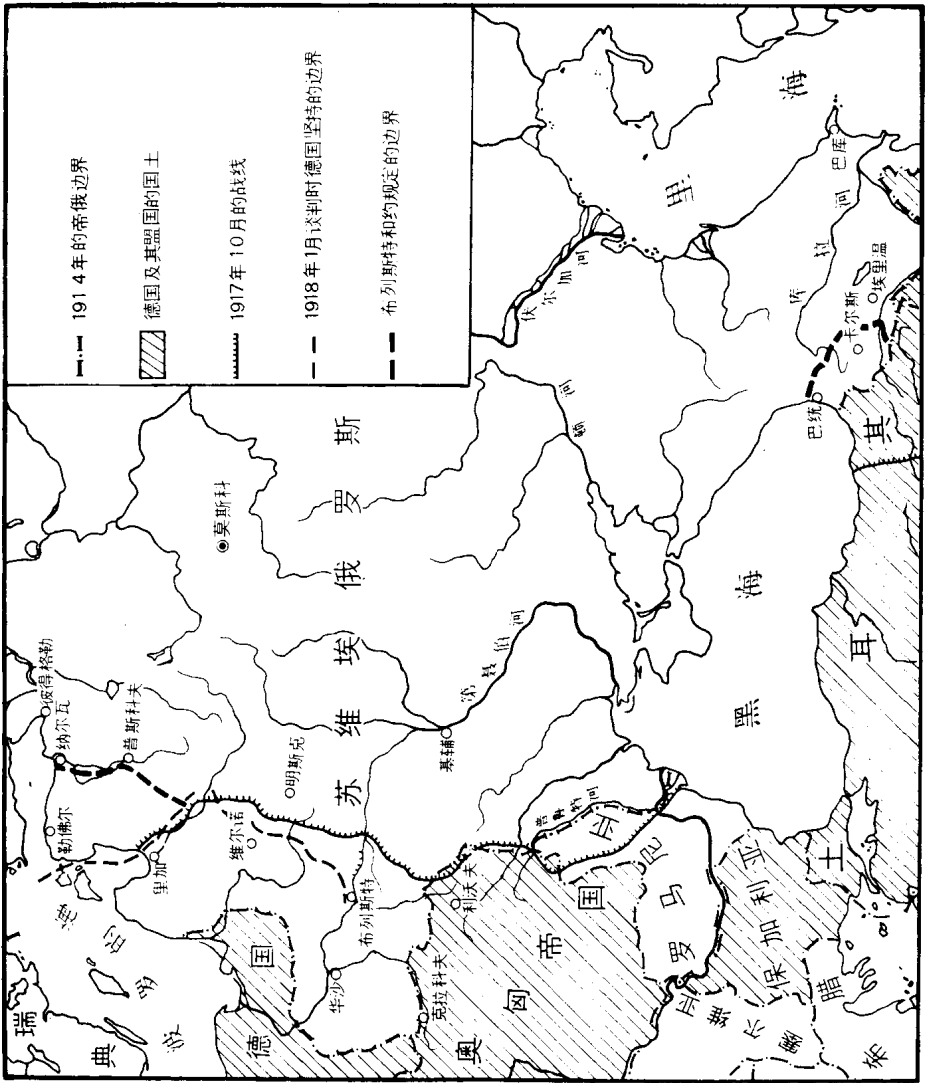
彼得格勒十月武装起义

(一九一七年十一月)



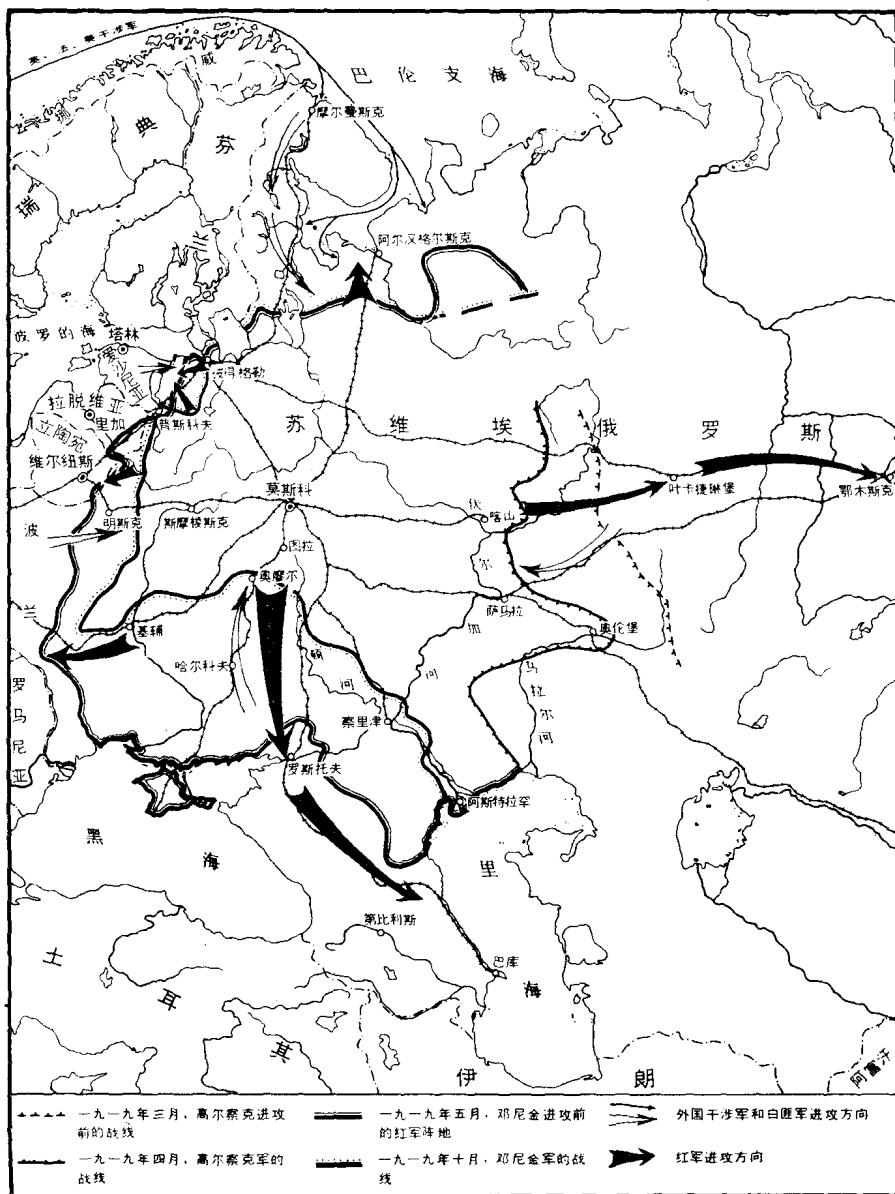
芬 兰 湾

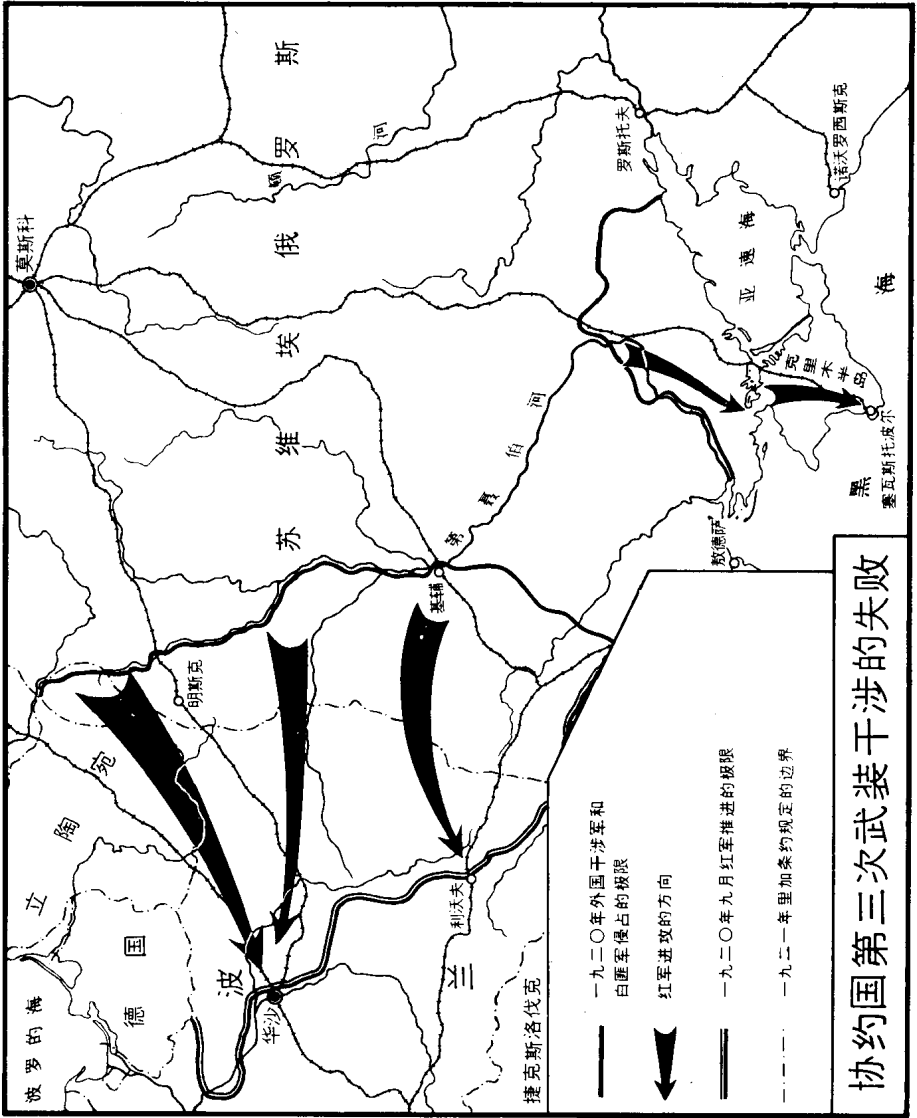
-  起义的领导中心
-  成立赤卫队的主要地点
-  彼得格勒驻军中的革命部队
-  俄国的存残政府
-  列宁在十一月六日去斯莫尔尼宫的路线
-  革命队伍进攻的主要路线
-  反革命的主要据点
-  向冬宫的总进攻



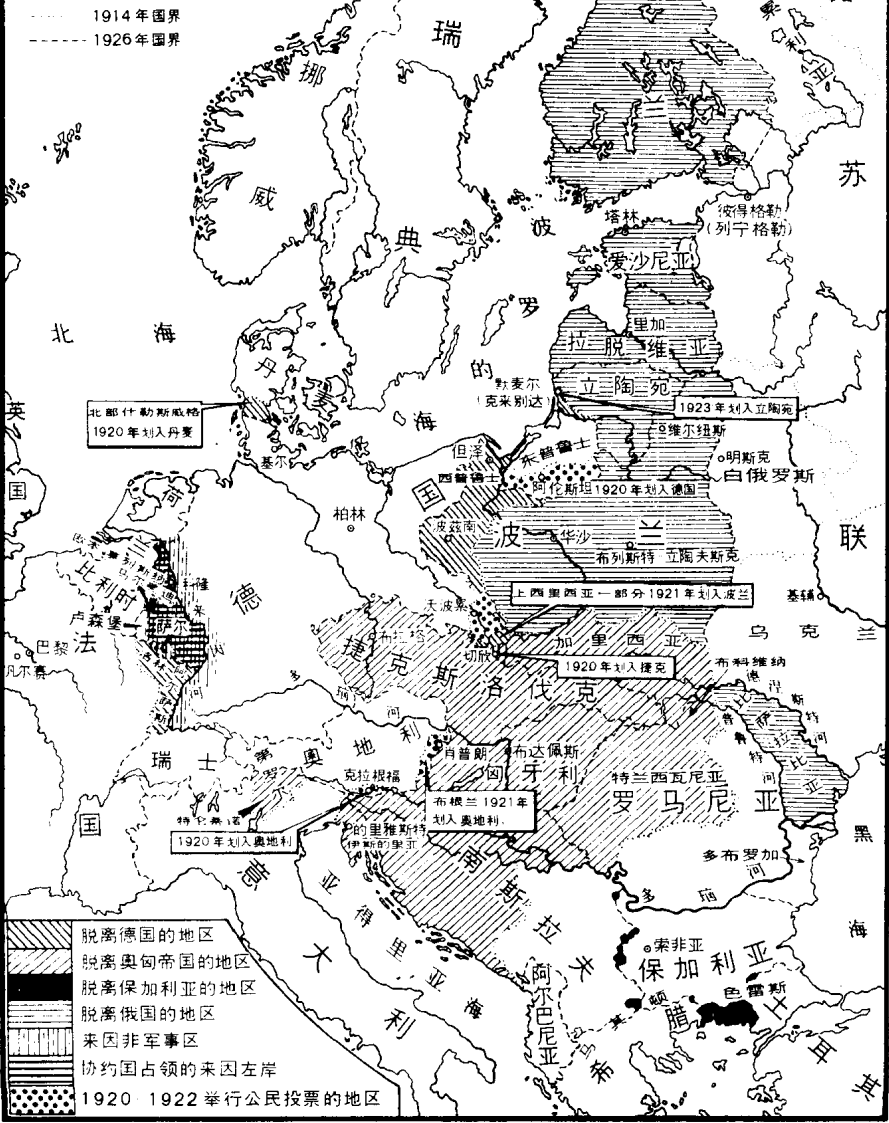
布列斯特和约(一九一八年三月三日)

协约国第一、二次武装干涉的失败

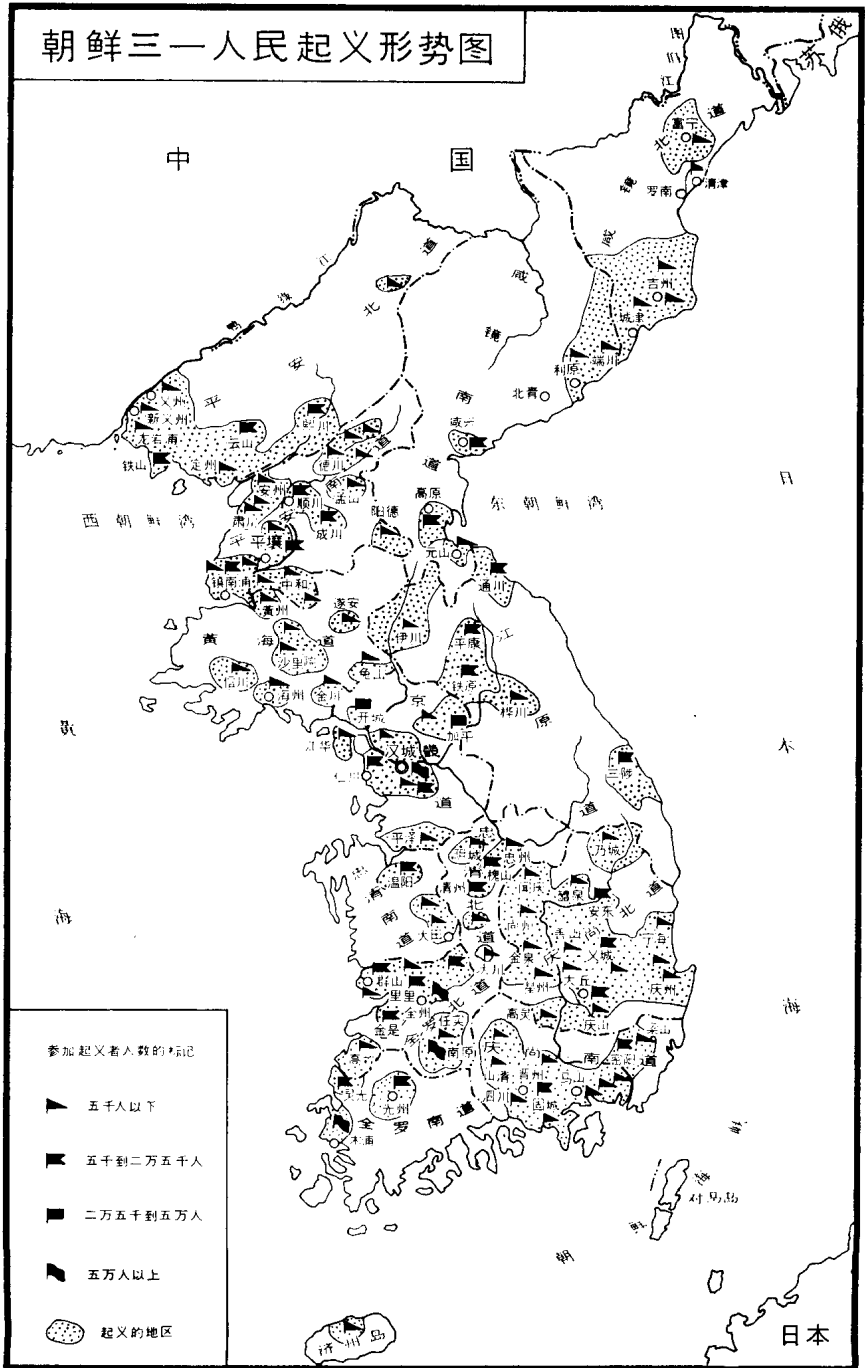




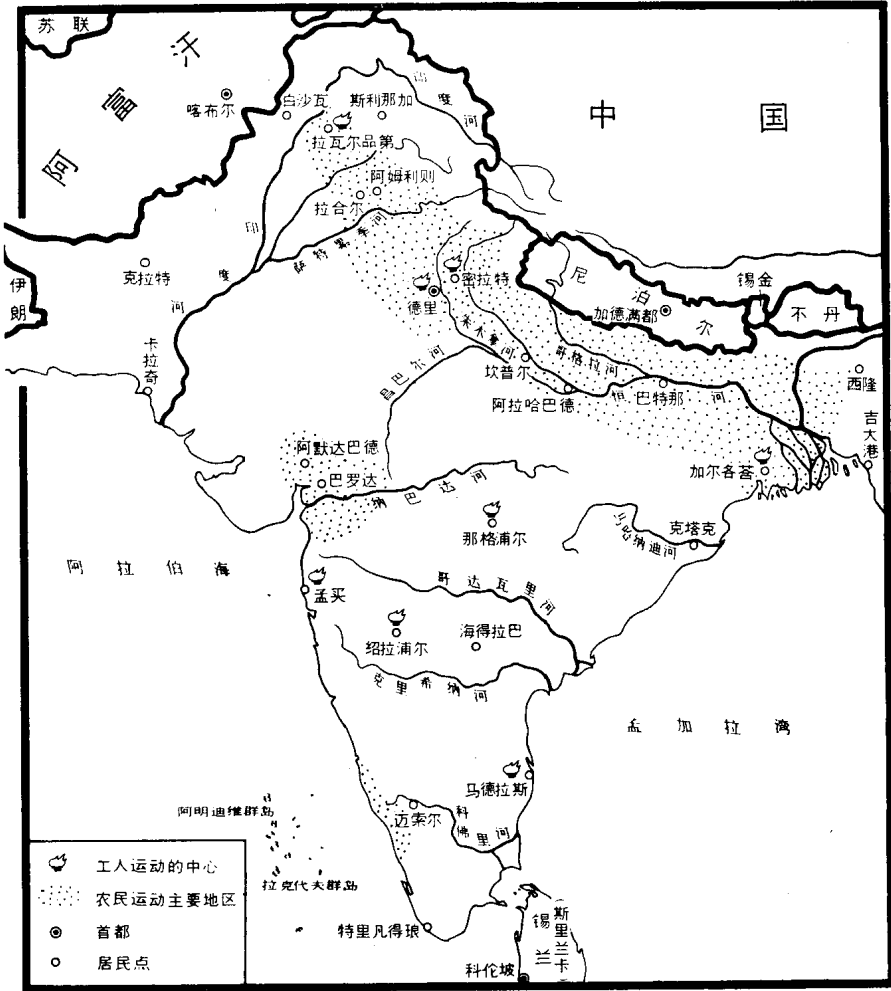
凡尔赛和约后欧洲疆界的变化



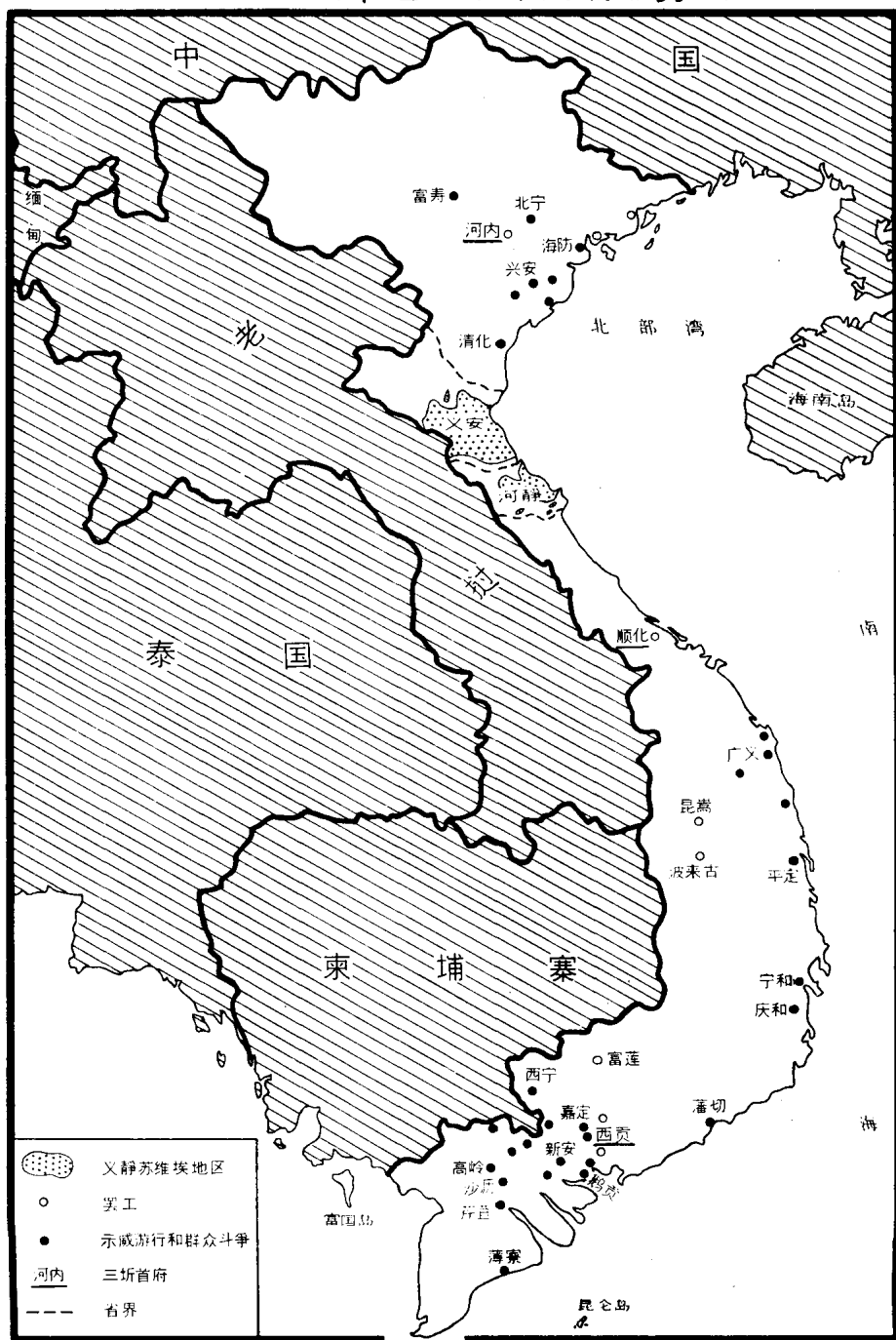
朝鲜三一人民起义形势图



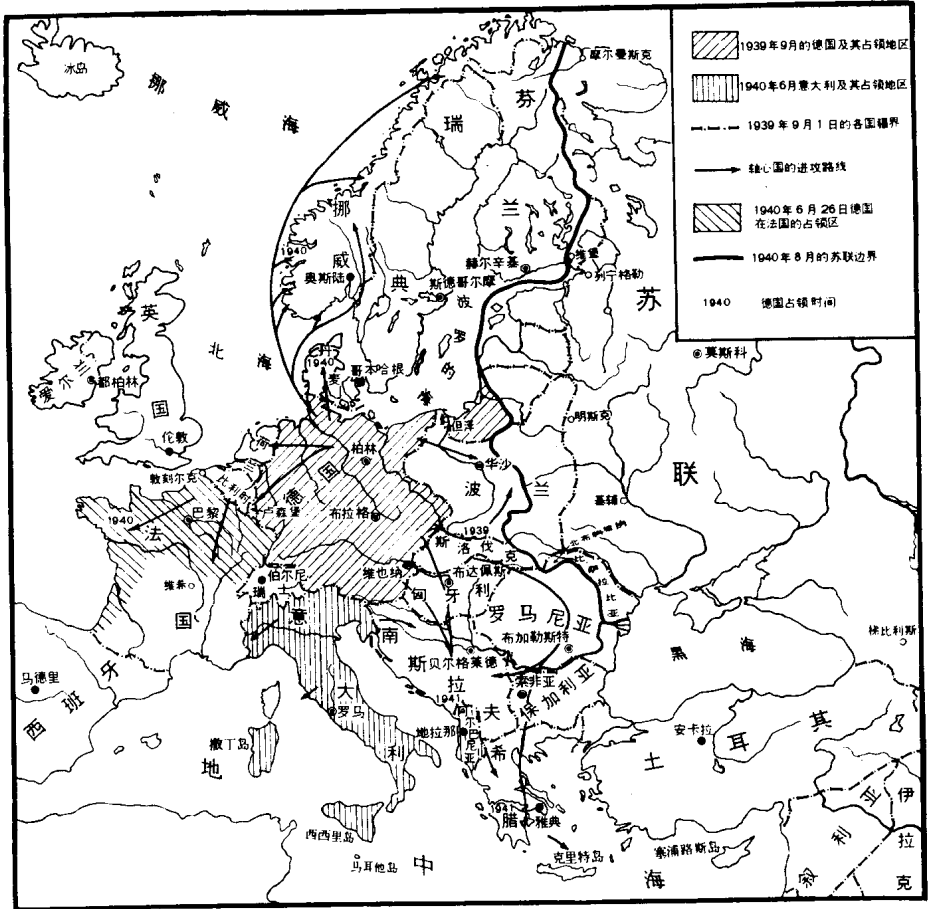
印度的民族解放运动 (1919—1929年)



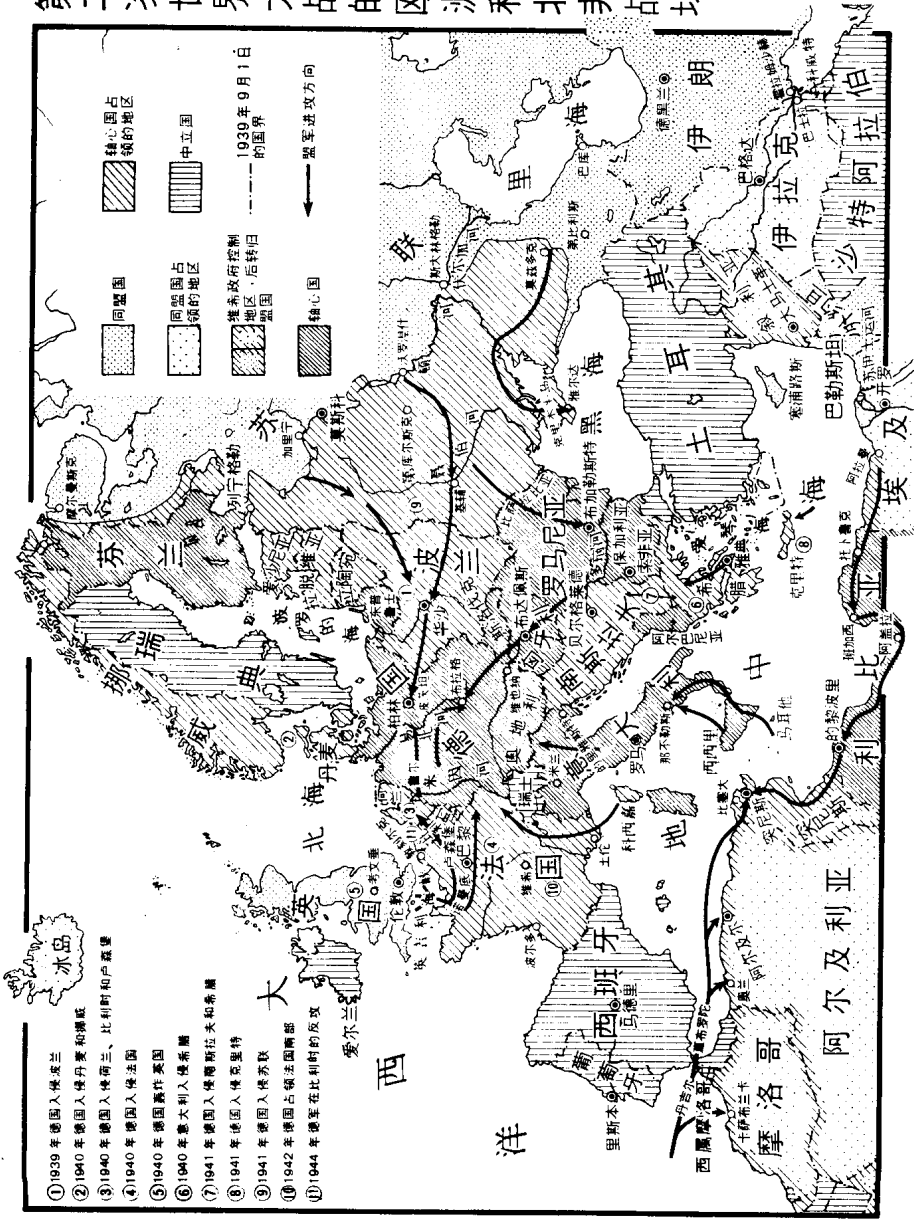
1930-1931年越南革命高潮形势图



1939年9月至1941年6月欧洲形势



第二次世界大战的欧洲和北非战场



第二次世界大战的太平洋战场

